République Démocratique du Congo

Projet de Développement Multisectoriel et de Résilience Urbaine deKinshasa (KIN-ELENDA)

Mise en place d'un répertoire automatisé des contribuables aux impôts fonciers, impôts sur les revenus locatifs et taxe d'assainissement, ainsi que la mise en place d'un système efficient de collecte de recettes communales

DP n°010/MITP/CI/KIN-ELENDA/2024

Rapport technique sur la mise en place du répertoire automatisé des contribuables aux impôts fonciers, impôts sur les revenus locatifs et taxe d'assainissement de la Direction Générale des Recettes de la Ville-Province de Kinshasa
(Rapport étape 2)

Janvier 2026

République Démocratique du Congo

Projet de Développement Multisectoriel et de Résilience Urbaine deKinshasa (KIN-ELENDA)

Mise en place d'un répertoire automatisé des contribuables aux impôts fonciers, impôts sur les revenus locatifs et taxe d'assainissement, ainsi que la mise en place d'un système efficient de collecte de recettes communales

Rapport technique sur la mise en place du répertoire automatisé des contribuables aux impôts fonciers, impôts sur les revenus locatifs et taxe d'assainissement de la Direction Générale des Recettes de la Ville-Province de Kinshasa
(Rapport étape 2)

Janvier 2026

Propriété du document

Auteur(s)	**Simon Kanduki,** Chef de mission, expert en finance publique **Mohamed Ben Nasr,** Expert en Systèmes informatiques **KAKALA BAHONGELA Rudy,** Expert 2 en fiscalité locale **LUTONADIO KABEYA Sam,** Spécialiste en SGBD **MBUKU MAYUKU Yanick,** Expert foncier
E-mail	mehdi.fazaa@ccm-cg.com implementation@ccm-cg.com
Référence	P-000636
Version	1.00
Statut	Rapport technique sur la mise en place du répertoire automatisé des contribuables aux impôts fonciers, impôts sur les revenus locatifs et taxe d'assainissement de la Direction Générale des Recettes de la Ville-Province de Kinshasa
Date du document	Janvier 2026
Nombre de pages	75 pages

Approuvé par

Nom	**Mehdi Fazaa**
Fonction	Project Manager - Expert d'appui

Pour les aspects contractuels, commerciaux et de réalisation, veuillez prendre contact avec :

Nom	**Imad Chamas**
Fonction	Managing Partner
Adresse	Rond-point Schuman 2-4 - 1040 - Bruxelles
Téléphone	+32 2 403 36 61
E-mail	imad.chamas@ccm-cg.com

Liste des abréviations

Abréviation	Signification
API	Interface de Programmation Applicative
COTS	Commercial Off-The-Shelf (progiciel du marché)
DAO	Dossier d'Appel d'Offres
DGRK	Direction Générale des Recettes de Kinshasa
DGI	Direction Générale des Impôts
ETL	Extract-Transform-Load (processus d'intégration de données)
GUCE	Guichet Unique de Création d'Entreprise
GIS	Geographic Information System (équivalent anglais de SIG)
IF	Impôt Foncier (propriétés bâties et non bâties)
IRL	Impôt sur les Revenus Locatifs
KPI	Indicateur Clé de Performance
NIF	Numéro d'Identification Fiscale
OTP	One-Time Password (mot de passe à usage unique)
PKI	Public Key Infrastructure (infrastructure à clés publiques)
PNG	Portail Numérique du Contribuable (si mentionné comme portail)
RBAC	Role-Based Access Control (contrôle d'accès par rôle)
REGIDESO	Régie de Distribution d'Eau
SIGREC	Système d'Information Géographique Fiscal de la DGRK
SIG	Système d'Information Géographique
SGBD	Système de Gestion de Base de Données
SLA	Service Level Agreement (engagements de service)
SMS	Short Message Service
SNEL	Société Nationale d'Électricité
TAS	Taxe d'Assainissement
TCO	Coût Total de Possession
UAT	User Acceptance Testing (tests d'acceptation utilisateurs)
VFE	Vérification/Fouille Externe (contrôle terrain)
VPK	Ville-Province de Kinshasa

Sommaire

1. Introduction 8
1.1 Rappel du contexte du Projet Kin-Elenda et lien avec l'étape de diagnostic 8
1.2 Problématique centrale et justification de l'intervention technique 9
1.3 Objectifs du présent rapport technique 9
1.4 Approche méthodologique 10
1.5 Limites, contraintes institutionnelles et techniques 12

2. Rappel des constats de l'évaluation 13
2.1 Bilan de performance 13
2.2 Constat majeur en termes de contraintes 14
2.2.1 Organisation administrative 14
2.2.2 Textes légaux et réglementaires 15
2.2.3 Rendement des actes générateurs (IF, IRL et taxe d'assainissement) 15
2.2.4 Organisation des registres des services cadastraux 15
2.2.5 Organisation du répertoire des contribuables des actes générateurs 16

3. Analyse fonctionnelle du répertoire existant 17
3.1 Modalités actuelles d'enregistrement des contribuables 17
3.2 Logique des titres de propriété 18
3.3 Règles d'identification du contribuable 19
3.4 Cohérence avec IF, IRL, TAS 19
3.5 Nomenclatures de l'IF, l'IRL et de la TAS et dispositions applicables 20
3.5.1 Impôt sur les propriétés foncières bâties et non bâties 20
3.5.2 Impôt sur les revenus locatifs 21
3.5.3 Taxe d'assainissement 21
3.5.4 Impôt foncier 22
3.5.5 Impôt sur les revenus locatifs 23
3.5.6 Taxe d'assainissement 23

4. Analyse technique du répertoire existant 24
4.1 Base de données et architecture existantes 24
4.2 Fragmentation des données et absence de centralisation 24
4.3 Interfaces, sources de données et processus d'alimentation 25
4.3.1 Interfaces inexistantes ou très limitées 25
4.3.2 Sources de données actuellement utilisées 25
4.3.3 Processus d'alimentation du répertoire 25
4.3.4 Niveau d'automatisation actuel 25
4.3.5 Contraintes d'infrastructure et d'outillage 26
4.3.6 Sécurité, droits d'accès et gouvernance technique 26
4.3.7 Contraintes méthodologiques et organisationnelles liées au volet technique 27

5. Proposition de conception fonctionnelle du répertoire cible (SIGREC) 28
5.1 Nouveau contenu des fichiers d'identification parcellaires 28
5.1.1 Principes 28
5.1.2 Identification complète de la parcelle 29
5.1.3 Parcelle comme enregistrement unique de référence 30
5.1.4 Effets attendus de cette approche 30
5.2 Urbanisation du système SIGREC cible 30
5.3 Schéma fonctionnel 31
5.4 Architecture applicative 32
5.4.1 Module de gestion des référentiels (parcelles, bâtiments, unités, contribuables) 33

5.4.2 Module de gestion de l'assiette (IF - IRL - TAS) ... 34
5.4.3 Module de gestion des droits et exonérations ... 35
5.4.4 Module de gestion des mutations foncières ... 37
5.4.5 Module de workflow d'enrôlement et de validation ... 38
5.4.6 Module de contrôle et inspection terrain ... 39
5.4.7 Module de gestion des déclarations et auto-déclarations ... 41
5.4.8 Module de calcul et de liquidation ... 42
5.4.9 Module d'émission des titres et notifications ... 43
5.4.10 Module de contentieux et sanctions ... 45
5.4.11 Module de cartographie SIG et analyses spatiales ... 48
5.4.12 Module d'aide à la décision ... 49
5.4.13 Conclusion de la conception fonctionnelle ... 50
5.5 Schéma des données ... 51
5.5.1 Nouveau contenu des fichiers d'identification parcellaires ... 51
5.5.2 Champs essentiels (NIF, Statuts, foncier, type de propriété) ... 51
5.5.3 Structuration des données : parcelle, contribuable et relations associées ... 51
5.5.4 Processus d'actualisation et de sécurisation des données ... 53
5.5.5 Actualisation continue (recensement roulant) ... 53
5.5.6 Flux d'échanges institutionnels ... 53
5.5.7 Sécurisation et audit ... 54

6. Architecture technique du répertoire cible (SIGREC/DGRK) ... 55
6.1 Principes directeurs de la conception technique ... 55
6.2 Architecture technique et applicative globale ... 56
6.3Architecture des données, interopérabilité et échanges ... 57
6.4 Architecture d'infrastructure et interconnexion des sites ... 59
6.5 Sécurité, continuité de service et sauvegarde ... 60

7. Scénarios de mise en œuvre du répertoire SIGREC ... 62
7.1 Tableau comparatif des scénarios de mise en œuvre du répertoire SIGREC ... 63
7.2 Scénario recommandé ... 64

8. Dispositions complémentaires ... 65
8.1 Renforcement des capacités et formation ... 65
8.2 Gestion du changement et communication ... 65
8.3 Appui logistique et équipements ... 65
8.4 Aspects juridiques et réglementaires ... 66
8.5 Suivi, évaluation et indicateurs de performance ... 66
8.5.1 Tableau de bord opérationnel ... 66
8.5.2 Mécanismes de reporting ... 67
8.6 Risques et hypothèses ... 67
8.6.1 Hypothèses de réussite ... 67
8.6.2 Principaux risques identifiés ... 67

9. Cadre de mise en œuvre et de suivi des actions planifiées ... 69
9.1 Instruments de mise en œuvre ... 69
9.1.1 Feuille de route opérationnelle et budgétisée ... 69
9.1.2 Plan de communication ... 69
9.1.3 Acteurs de mise en œuvre ... 70
9.1.4 Leadership politique et pilotage stratégique à court terme ... 70
9.1.5 Comité de pilotage et articulation avec les cadres nationaux de réforme ... 70
9.1.6 Administration fiscale provinciale (DGRK) ... 70
9.1.7 Services fonciers et de l'habitat ... 71
9.1.8 Partenaires du projet et acteurs externes ... 71

9.2 Mécanismes de suivi-évaluation 71
9.2.1 Dispositif et principes de suivi-évaluation 71
9.2.2 Outils de suivi-évaluation 71
9.2.3 Instance de suivi-évaluation 71
9.2.4 Acteurs et responsabilités du suivi-évaluation 72
9.3 Conditions de succès et facteurs de risque 72
9.3.1 Conditions de succès 72
9.3.2 Facteurs de risque 72
9.3.3 Mesures de mitigation des risques 72
9.4 Feuille de route 72
9.4.1 Principes de structuration 72
9.4.2 Chronologie indicative (recalée) 73
9.4.3 Activités de continuité post-projet 73
9.4.4 Cadre financier, soutenabilité et valeur ajoutée 73

10. Conclusion et perspectives 75
10.1 Conclusion 75
10.2 Synthèse des résultats attendus 75
10.3 Prochaine étape 75
10.3. Validation institutionnelle 75
10.3.2 Mobilisation des ressources 75

Liste des tableaux :

Tableau 1: Synthèse des limites et contraintes identifiées 12
Tableau 2: Synthèse des principaux constats techniques 27
Tableau 3 : Nouveau contenu des fichiers d'identification parcellaires 51
Tableau 4 : Champs de la parcelle (entité principale) 52
Tableau 5 : Champs du contribuable / propriétaire 52
Tableau 6 : Lien entre parcelle et contribuable 52
Tableau 7 : Comparatif des scénarios de mise en œuvre du répertoire SIGREC 63
Tableau 8 : Indicateurs clés de performance (KPI) 66
Tableau 9 : Principaux risques 68
Tableau 10 : Analyse des risques 72
Tableau 11 : Mesures de mitigation 72
Tableau 12 : Chronologie de mise en œuvre 73
Tableau 13 : Estimation indicative CAPEX / OPEX 73

Liste des figures:

Figure 1 : Urbanisation du système SIGREC cible 31
Figure 2 : Schéma fonctionnel du système cible 32
Figure 3 : Architecture applicative 33
Figure 4 : Processus d'actualisation et de sécurisation des données 53

1. Introduction

1.1 Rappel du contexte du Projet Kin-Elenda et lien avec l'étape de diagnostic

Le projet de développement KIN ELENDA a comme objectif de concourir à l'amélioration de la capacité institutionnelle en matière de gestion urbaine et d'accès aux infrastructures et services, ainsi qu'aux opportunités socio-économiques en Ville province de Kinshasa.

La Sous composante 2.3. « Gouvernance locale » de ce projet a pour objectif de renforcer les capacités de la Ville de Kinshasa et des communes pilotes en vue d'améliorer la qualité des services publics délivrés à la population. De façon spécifique, la sous-composante vise à renforcer les capacités locales, notamment en matière de mobilisation des recettes, planification des investissements, gestion financière et fourniture de services publics. Elle appuie les réformes de gouvernance en amont et en aval, en se concentrant sur le niveau provincial mais en incluant également certaines communes. Cette sous-composante se concentre sur les améliorations fondamentales de la gestion des recettes et des dépenses, l'amélioration de la gestion et de l'organisation des ressources humaines ainsi que le renforcement de la responsabilité et de la transparence. Elle consiste en plusieurs volets, dont :

i) La maximisation et sécurisation des recettes, visant l'optimisation du potentiel fiscal au niveau de la VPK ainsi qu'au niveau communal.

ii) Le renforcement des capacités, visant à améliorer les procédures de gestion administrative et financière de la ville province de Kinshasa (VPK) et des communes et à renforcer leurs capacités matérielles et humaines.

Pour la VPK Les activités de maximisation des recettes devront permettre l'amélioration du niveau des recettes nécessaires pour renforcer son autonomie financière et sa capacité de bonne gouvernance et de financer le développement des infrastructures et la fourniture des services publics.

Pour ce volet, les objectifs de l'assistance technique de la 1ère phase consistent en :

a) l'évaluation du système actuel (partiellement modernisé) de gestion de l'assiette des impôts et taxes du secteur foncier de la VPK, notamment l'impôt sur les propriétés foncières bâties et non bâties (IF), l'impôt sur les revenus locatifs (IRL) et la Taxe d'assainissement (TAS) et, en fonction des résultats de cette évaluation,

b) la mise à jour de la conception d'un répertoire des contribuables à ces différents impôts.

Les objectifs spécifiques liés à ce volet, et spécifiquement à l'automatisation du répertoire des contribuables, sont les suivants :

a) Evaluer l'efficacité et l'efficience de l'outil de gestion en place pour la collecte des impôts et taxe du secteur foncier urbain précités et en évaluer le potentiel fiscal du secteur ;

b) Définir les caractéristiques de l'application informatique ainsi que du matériel requis pour l'implémentation d'une base des données destinée à la gestion des opérations d'assiette et de recouvrement de toutes les taxations urbaines ;

c) Procéder à une évaluation quantitative et qualitative des matériels utiles à la numérisation de toute la documentation cadastrale et foncière utile pour une fiabilisation des opérations de taxation foncière ;

Dans le cadre de la mise en œuvre de ce volet de la mission, relativement aux termes du contrat d'assistance technique, le rapport relatif à la première étape qui consiste à l'évaluation du système actuel de gestion de l'assiette des impôts et taxes du secteur foncier de la VPK, notamment l'impôt sur les propriétés foncières bâties et non bâties (IF), l'impôt sur les revenus locatifs (IRL) et la Taxe d'assainissement (TAS) a été soumis. Le présent rapport technique concerne la proposition de la conception fonctionnelle et technique d'une base des données destinée à la gestion des opérations d'assiette sous forme mise à jour du répertoire automatisé à place des contribuables aux actes générateurs précités.

1.2 Problématique centrale et justification de l'intervention technique

Le défi actuel de la Ville province de Kinshasa demeure l'accroissement de ses recettes propres au regard de son potentiel fiscal tel qu'il ressort de la nomenclature des impôts et autres actes générateurs relevant des compétences fiscales exclusives dont elle jouit. Le secteur foncier, un des plus grands secteurs générateurs des recettes fiscales et non fiscales de la Ville de Kinshasa, loge un potentiel fiscal immense qui, rationnellement exploité, peut être à la base d'importants revenus fiscaux et non fiscaux pour la VPK. Cela justifie la raison pour laquelle il a été retenu parmi les axes prioritaires de ses réformes.

Le système fiscal en vigueur en RD Congo étant déclaratif, au vu du nombre de contribuables qui sont répertoriés et fiscalisés par rapport au portefeuille potentiel des contribuables aux actes précités, il se dégage l'amer constat d'un écart abyssal entre les deux réalités dont ne peut venir à bout le système de détection des contribuables non enregistrés par voie de recherche et recoupement actuellement en place au sein de la DGRK.

En cette matière, la DGRK gagnerait en efficacité et en efficience en combinant croisement des données des sources secondaires (services cadastraux et habitat, DGI, REGIDESO, SNEL, etc.) et opérations de recensement des contribuables sur terrain, actions qui concourraient à renforcer la gestion de l'assiette fiscale provinciale. Malheureusement il se dégage les constats ci-après :

La Ville de Kinshasa compte 13 circonscriptions foncières ; chacune de ces circonscriptions foncières urbaines compte 2 divisions : le cadastre et la conservation des titres immobiliers. Les recettes fiscales et non fiscales liées au domaine géré par ces administrations provinciales sont constituées de l'impôt foncier et de l'impôt sur les revenus locatifs ainsi que des taxes dont la gestion est totalement déconnectée du système de gestion cadastrale en place. Ce dernier étant assurée manuellement, est déconnecté du système fiscal en cours de digitalisation pour la VPK. Les 13 circonscriptions foncières que compte la VPK disposent des plans à grande échelle reprenant le découpage parcellaire dont la mise à jour est assurée manuellement. Chaque parcelle a un dossier technique regroupant l'historique de l'ensemble des documents la concernant mais dont les opérations de mise à valeur, de mutation ou d'utilisation sont difficilement retraçable du point de vue fiscal. Bref, les deux systèmes de gestion fonctionnent dos à dos. Le constat est le même pour d'autres services étatiques pouvant disposer d'autres informations utiles à la fiscalisation comme les divisions de l'habitat et notariats communaux pour les IRL.

Par ailleurs, les systèmes informatiques de gestion du répertoire des contribuables de la DGRK ne sont pas interconnectés avec ceux des autres services potentiellement pourvoyeurs d'informations sur les contribuables (REGIDESO, SNEL, etc.).

Le constat sur terrain est que les initiatives prises au sein de la DGRK en termes d'actions qui concourent à la détection des contribuables non enregistrés en vue de renforcer le système fiscal provincial en matière d'IF, d'IRL et de la taxe d'assainissement sont sporadiques.

1.3 Objectifs du présent rapport technique

L'objectif général du présent rapport technique est de définir une conception actualisée, complète et opérationnelle du répertoire automatisé des contribuables assujettis à l'impôt foncier (IF), à l'impôt sur les revenus locatifs (IRL) et à la taxe d'assainissement (TAS). Cette conception repose sur la mise en place d'un Système d'Information Géographique Fiscal (SIGREC) qui assure l'intégration des dimensions fiscale, cadastrale et spatiale. Le rapport vise à doter la DGRK d'un outil moderne permettant d'identifier, recenser, géolocaliser et suivre de manière fiable l'ensemble des contribuables et des biens imposables. Cet outil devra être exhaustif, sécurisé, interopérable et géolocalisé, tout en étant conforme aux bonnes pratiques internationales en matière d'administration fiscale, notamment celles recommandées par la méthodologie TADAT pour l'intégrité du registre des contribuables.

De manière spécifique, le rapport poursuit les objectifs suivants :

- **Définir le modèle fonctionnel cible du répertoire des contribuables**, en précisant les processus d'identification, d'enregistrement, de mise à jour, de suspension et de radiation des contribuables et des biens imposables ;

- **Décrire le modèle de données du futur système**, intégrant les informations fiscales, cadastrales, foncières et géographiques, afin d'assurer la correspondance entre parcelle, contribuable et obligation fiscale ;
- **Proposer une architecture technique moderne et évolutive**, incluant une base de données spatiale, des applications web et mobiles, et des mécanismes de haut niveau de disponibilité et de sécurité ;
- **Définir les sources d'alimentation du répertoire**, notamment la migration des bases existantes, les opérations de recensement géolocalisé et les échanges de données avec les institutions partenaires ;
- **Mettre en place des mécanismes de contrôle d'intégrité et d'unicité**, permettant de détecter et corriger les doublons, incohérences, anomalies déclaratives et enregistrements inactifs ;
- **Décrire les modalités d'intégration de la géolocalisation**, y compris la capture des coordonnées GPS et la gestion cartographique des parcelles et activités économiques ;
- **Préciser le lien fonctionnel et technique avec le cadastre et les services fonciers**, afin d'assurer le suivi des mutations et la sécurisation des titres de propriété ;
- **Proposer des options de mise en œuvre technique et organisationnelle**, en analysant les coûts, les délais, les risques et les exigences en matière d'infrastructure ;
- **Définir le cadre institutionnel et organisationnel de déploiement**, en précisant les rôles et responsabilités des acteurs impliqués au niveau provincial et communal ;
- **Élaborer une feuille de route opérationnelle**, décrivant les étapes de mise en œuvre à court et moyen terme, les priorités, les livrables attendus et les prérequis techniques ;
- **Proposer un plan de renforcement des capacités**, visant la formation des agents, l'appropriation du système et la pérennisation des compétences techniques au sein de la DGRK ;
- **Prévoir les dispositifs de suivi-évaluation et de gouvernance du projet**, afin d'assurer le pilotage, la qualité des données et la durabilité du répertoire automatisé.

1.4 Approche méthodologique

Sur base des informations recueillies et des recommandations préliminaires formulées dans le diagnostic, l'approche de mise à jour du système de gestion de l'assiette des contribuables suivra les étapes suivantes :

- ***La proposition d'une solution informatique d'établissement du registre/répertoire des contribuables ;***
- ***Mise à jour du répertoire existant (actualisation des données du répertoire) ;***

Le résultat souhaité est que la solution proposée soit compatible aux bonnes pratiques internationalement admises telles que énoncées par le guide TADAT en ce qui concerne le domaine d'analyse DA1 relatif à l'intégrité de la base du registre des contribuables : L'immatriculation des contribuables et la tenue d'un registre exact et exhaustif sont essentiels pour le bon fonctionnement d'une administration fiscale[1].

Pour atteindre le résultat souhaité, la conception devra tenir compte des bonnes pratiques adoptées universellement par les administrations fiscales à savoir :

(i) Utilisation d'un numéro d'identification unique du contribuable (NIF) qui facilite l'identification de routine des contribuables pour les actions administratives (par exemple, la détection des défaillants déclaratifs), la communication d'informations à des tiers et le croisement des données ;

(ii) Base de données contenant des informations d'identification suffisantes, précises et fiables (par exemple, le nom, l'adresse, les coordonnées, la nature et la taille de l'activité commerciale, et les obligations fiscales par type d'impôt) ;

(iii) Identifier et signaler les dossiers temporairement inactifs ;

[1] *TADAT est un outil conçu pour fournir une évaluation objective des forces et des faiblesses des éléments clés du système d'administration fiscale d'un pays, en se référant à neuf « Domaines d'analyse » (DA). Les résultats de l'évaluation présentent l'ampleur de la réforme nécessaire et les priorités relatives à retenir.*

Le système devra permettre :

A. *D'assurer la pertinence des informations sur les contribuables enregistrés et la qualité du répertoire aux fins d'échanges avec les contribuables et les intermédiaires fiscaux*. A cet effet, on devra s'assurer que :

1) Les informations contenues dans la base de données du répertoire comprennent, au minimum, le nom complet du contribuable, son adresse physique, ses coordonnées (le numéro de contact, l'adresse mail ou professionnelle d'un contribuable), sa date de naissance ou de constitution, la nature de son activité commerciale, l'identité des entités associées et des parties liées au contribuable (par exemple, les actionnaires et/ou les filiales), la catégorie de contribuable, le secteur économique/industriel, ainsi que les obligations de dépôt et de paiement applicables aux impôts de base pour lesquels le contribuable est immatriculé et en priorité l'IF, l'IRL et la Taxe d'assainissement.

2) La base de données du répertoire informatisée est centralisée.

3) Chaque contribuable répertorié possède un numéro d'identification unique à forte intégrité.

4) Le sous-système informatique d'enregistrement dans le répertoire :
- Constitue une interface avec d'autres sous-systèmes informatiques (par exemple, traitement des dossiers et des paiements).
- Permet au personnel de première ligne d'avoir une vue d'ensemble des données d'identification et autres détails d'un contribuable pour les impôts et taxe ciblés.
- Permet de désactiver ou de radier les contribuables et d'archiver les informations de manière à pouvoir les restaurer en cas de besoin.
- Génère des informations de gestion liées à l'enregistrement (par exemple, des statistiques sur les contribuables immatriculés par type d'impôt/taxe, localisation et secteur économique).
- Fournit aussi des pistes de vérification de l'accès utilisateurs et des modifications apportées aux données des contribuables.
- Utilise les données d'immatriculation du contribuable pour générer des déclarations fiscales.
- Offre aux entreprises (personnes morales) et aux particuliers immatriculés (disposant d'un NIF) un accès en ligne sécurisé leur permettant de s'enregistrer et, une fois enregistrées, de mettre à jour les informations contenues dans la base de données (par exemple, le numéro de contact, l'adresse mail ou professionnelle d'un contribuable).

B. *De garantir l'exactitude des informations contenues dans le répertoire des contribuables*. A cet effet, on devra s'assurer que le système permet de:

1) Identifier et supprimer les contribuables inactifs (par exemple, les personnes décédées et les entreprises en faillite), les doublons et les faux déclarants et invalides de la base de données et désactiver et marquer les dossiers temporairement inactifs ;

2) Vérifier l'exactitude des informations contenues dans la base de données du répertoire, notamment en recourant à des processus de leur recoupement à grande échelle avec les informations des bases de données d'autres agences gouvernementales telles que la DGI, la SNEL, la REGIDESO, le GUCE.

C. *De détecter les contribuables potentiels non répertoriés*

A cet effet, on devra s'assurer que le système permet la prise des initiatives pour détecter, identifier, enregistrer et fiscaliser les personnes morales, les entreprises et les particuliers non répertoriés par voie d'interopérabilité et de croisement des données issues de sources d'information tierces (DGI, la SNEL, la REGIDESO, le GUCE) et d'emploie des dispositifs automatisés de recensement des contribuables et de géolocalisation des biens imposable.

1.5 Limites, contraintes institutionnelles et techniques

Les travaux de diagnostic ont été conduits dans un contexte institutionnel et opérationnel contraint. Plusieurs facteurs ont affecté la disponibilité et la qualité des informations nécessaires à l'analyse du système actuel, notamment l'accès limité à certaines bases de données, le caractère partiel des informations transmises et le calendrier resserré d'exécution. Les changements fréquents d'interlocuteurs au sein de la DGRK et du ministère des Finances, combinés à une faible sensibilisation de certains services à l'importance du diagnostic pour l'amélioration de leur propre gestion, ont également ralenti la collecte des données. En conséquence, certains constats et estimations reposent sur des informations incomplètes ou anciennes, ce qui introduit un biais méthodologique reconnu dans ce rapport.

Par ailleurs, bien que l'analyse ait parfois touché à des aspects plus larges du système de gestion fiscale, le périmètre du présent rapport technique demeure volontairement recentré sur la gestion automatisée de l'assiette fiscale pour l'impôt foncier (IF), l'impôt sur les revenus locatifs (IRL) et la taxe d'assainissement (TAS). Les dimensions relatives au recouvrement, au contentieux ou à la comptabilité publique ne sont pas développées ici, même si elles interfacent naturellement avec le répertoire des contribuables. Le système proposé est cependant conçu comme modulaire et interopérable, afin de permettre des extensions ultérieures vers d'autres sous-systèmes fiscaux.

Tableau 1: Synthèse des limites et contraintes identifiées

Domaine	Description synthétique de la contrainte	Impact sur le projet
Limites du diagnostic	Diagnostic partiellement fondé sur des données anciennes, parfois supérieures à dix ans, et sur des estimations de potentiel faute d'assiette vérifiée	Risque de sous-estimer l'ampleur réelle du recensement initial à mener et de dimensionner insuffisamment les ressources humaines et matérielles nécessaires
Contraintes institutionnelles	Absence de protocoles formalisés d'échange de données entre la DGRK, les circonscriptions foncières et autres administrations partenaires	Risque de non-coopération institutionnelle, difficulté de fiabilisation des titres et mutations, nécessité d'un arbitrage politique et de conventions formelles
Contraintes organisationnelles	Rotation fréquente des responsables, multiplicité d'intervenants, procédures peu normalisées et faible culture de gestion des données	Ralentissement des processus, hétérogénéité des pratiques, besoin important d'accompagnement au changement et de clarification des rôles
Contraintes techniques	Insuffisance d'équipements informatiques, alimentation électrique instable, absence d'infrastructures serveurs adaptées et connectivité limitée dans certains services	Menace sur la continuité de service, difficulté de déploiement du SIGREC, nécessité de renforcer au préalable l'infrastructure énergétique et informatique
Contraintes liées aux données	Données fragmentées, non géolocalisées, absence d'identifiant unique, coexistence de bases parallèles et fichiers manuels	Risques élevés de doublons, incohérences et erreurs, travaux importants d'assainissement et de migration des données à prévoir
Contraintes juridiques et réglementaires	Non-application systématique du NIF comme clé d'identification et absence de cadre clair pour l'interopérabilité des bases publiques	Limitation de l'efficacité du futur répertoire automatisé, nécessité d'appuis réglementaires complémentaires et de textes d'application

2. Rappel des constats de l'évaluation

Pour mieux appréhender l'état des lieux de l'organisation de la fiscalité au sein de la DGRK, et en particulier en ce qui concernes l'assiette fiscale de l'IF, l'IRL et la taxe d'assainissement, il sied de rappeler brièvement les constats clés de l'évaluation des performances du système en place.

Il sied de rappeler qu'en aout-septembre 2025, la DGRK a fait l'objet d'une évaluation TADAT dont le rapport a été rendu en septembre 2025 mais n'est pas encore publié au niveau du secrétariat TADAT. En ce qui concerne le Domaine d'analyse DA1 relatif à l'intégrité du registre des contribuables, l'évaluation a accordé la note D.

Dans cette partie, le diagnostic réalisé dans le cadre de notre mission dressant le bilan de performance globale de la DGRK l'ayant évaluée en termes d'efficacité dans la mobilisation des recettes tout en se focalisant sur la gestion de l'assiette fiscale en ce qui concerne l'intégrité du répertoire des contribuables à l'IF, l'IRL et la taxe d'assainissement, nous en rappelons les grandes lignes telles qu'elles ressortent dudit diagnostic, en présentant succinctement ses performances et ses contreperformances.

2.1 Bilan de performance

Les avancées majeures que le diagnostic a pu identifier à la faveur de l'organisation générale de la fiscalité au sein de la DGRK se résument en ce qui suit.

a) Organisation administrative
Il existe un cadre institutionnel organisant formellement l'administration fiscale qui consiste aux textes régissant les fonctions, responsabilités et tâches de ses agents. L'existence de job descriptions et d'un cadre organique témoigne de la structuration administrative en place.

La DGRK dispose de services spécialisés opérationnels (la Direction de gestion des impôts provinciaux et locaux (gestionnaire de l'IF et l'IRL personnes morales et grandes personnes physiques), la Direction de contrôle et de l'ordonnancement des recettes non fiscales (gestionnaire de la taxe d'assainissement personnes morales et grandes personnes physiques), la Direction Informatique) et son administration est implantée dans toutes les communes (en travers ses Directions de suivi des centres des recettes fiscales et non Fiscales), dans une position de proximité avec les contribuables.

Elle s'est également dotée d'une **Direction des Recherches et Recoupements (DRR),** structure dédiée à la détection des contribuables non enregistrés dotée d'une capacité avérée à identifier un volume important de contribuables (46 000 détectés lors d'une opération), un atout rare dans de nombreuses administrations infranationales.

b) Cadre légal et réglementaire régissant la fiscalité provinciale
Le diagnostic a noté l'existence des textes légaux au niveau national régissant la fiscalité en matière foncière et sur les revenus locatifs ainsi que d'assainissement ainsi qu'un cadre légal structuré consistant aux textes légaux (Edits) et réglementaires de portée provinciale portant application des dispositions de la législation nationale et qui s'arriment harmonieusement avec cette dernière, notamment l'Edit n° 005/2021 du 31 décembre 2021 portant réforme des procédures relatives à la perception des impôts, droits, taxes et redevances dus à la Ville de Kinshasa, les arrêtés provinciaux fixant les taux, modalités de perception et obligations des contribuables ainsi que les textes sectoriels relatifs à la taxation des déchets plastiques ou à l'assainissement..

c) Rendement des actes générateurs (IF, IRL et taxe d'assainissement)
Le diagnostic a noté les avancées ci-après concernant la mobilisation de ces ressources :

- Une performance budgétaire en voie d'amélioration pour l'IF et l'IRL.
- Un poids très prépondérant de l'IF et l'IRL dans l'ensemble des recettes de la province (39%). Les impôts sur la superficie des propriétés foncières bâties et non bâties (I.F) et sur les revenus locatifs (RL et IRL) génèrent une part très significative des recettes provinciales de la ville province de Kinshasa, en valeurs absolues comme en valeurs relatives, et on note une nette amélioration des réalisations par rapport aux prévisions, notamment pour l'IRL.

- La proportion des recettes des impôts fonciers et des impôts sur les revenus locatifs déclarées dans le délai sur la période est satisfaisante (en moyenne 86%).
- Des efforts sont en cours depuis 2024 pour la mobilisation de la « Taxe d'assainissement et enlèvement d'immondices ou ordures ménagères ».

d) Organisation du répertoire des contribuables des actes générateurs

Concernant l'organisation du répertoire des contribuables, les performances notées sont les suivantes :

- La DGRK a développé un système informatique **modulaire** de gestion de sa fiscalité qui dispose d'interfaces entre les différents sous-systèmes informatiques, gère les actions de manière séparée mais interconnectée permettant une communication fluide entre les modules (déclarations, paiements, suivi des défaillants, gestion des débiteurs, etc.) afin de faciliter l'exécution et le suivi efficace des opérations fiscales et l'usage (limité mais réel) de la télédéclaration. Les évidences empiriques en sont :
  - l'existence d'une plateforme web « e-dgrk » dédié à la gestion de la fiscalité, lequel constitue un point de départ pour automatiser le répertoire, car ayant familiarisé les agents à l'outil informatique et constituant une facilité dans la transition vers un nouvel outil numérique plutôt que de partir de zéro;
  - une Direction informatique fonctionnelle avec des services techniques opérationnels ;
  - la présence d'ordinateurs et modems dans les directions opérationnelles ;
  - la présence des agents déjà initiés à l'enregistrement numérique qui sont disséminés dans les différents services des directions opérationnelles.

- Elle dispose d'une base de données informatisée contenant un répertoire centralisé de ses contribuables assujettis aux impôt, droit, taxes et redevances relevant de la compétence provinciale, notamment à l'impôt foncier, à l'impôt sur les revenus locatifs et à la taxe d'assainissement dont l'Informatisation des répertoires est partiellement fonctionnelle.

e) Organisation des registres des services cadastraux et tenue des plans de lotissement, plans cadastraux, calques pouvant appuyer l'enrichissement du répertoire des assujettis à l'impôt foncier, à l'impôt sur les revenus locatifs et à la taxe d'assainissement

Le diagnostic a noté les opportunités suivantes au sein des circonscriptions foncières de la ville de Kinshasa :

- Existence sous format manuel (ou numérisé de manière ponctuelle) des plans de lotissement, plans cadastraux et calques attestée ;
- Existence au sein des services cadastraux des registres contenant des informations critiques pour l'assiette, telles que transferts de contrats de location, dossiers de nouvelles constructions, les mutations, conversions, morcellements, et autres opérations qui, dans un système intégré, devraient être automatiquement transmises à l'administration fiscale ;
- Les actes de taxation (constatation, liquidation, ordonnancement, paiement puis apurement) découlant de ces opérations peuvent constituer une base solide pour renforcer le répertoire des contribuables à l'impôt foncier si des mécanismes techniques et organisationnels d'interopérabilité étaient mis en place.

2.2 Constat majeur en termes de contraintes

A l'inverse des performances constatées, plusieurs faiblesses constitutives de contraintes d'ordre institutionnel et juridique ainsi que certaines faiblesses et limites liées au système de gestion du répertoire actuel ont été identifiées. Les lignes qui suivent en relèvent brièvement les plus pertinents :

2.2.1 Organisation administrative

Conforme aux standards actuels d'une administration fiscale modernisée et à l'évolution de la réforme des finances publiques en RD Congo plusieurs défis ont été relevés :

- Les textes administratifs existant sont obsolètes et requièrent une adaptation aux évolutions de la législation fiscale et aux réalités actuelles du terrain ;
- Les effectifs définis par le cadre organique sont dépassés, ;

- Dans certaines directions, notamment l'Informatique, le fonctionnement repose essentiellement sur un nombre très réduit d'agents qualifiés et certains postes stratégiques ne sont plus occupés.
- Certains services, notamment la Direction de Recherche et Recoupements (DRR), ont subi des transformations institutionnelles sans mise à jour correspondante des documents officiels ;

2.2.2 Textes légaux et réglementaires

De manière générale, si les textes légaux organisant l'impôt foncier et l'IRL en ville province de Kinshasa accusent une relative complétude, il a été noté la non-application systématique de l'obligation légale d'utiliser le **numéro d'identifiant fiscal (NIF),** clé unique d'identification répondant au standard international en matière de sécurisation des recettes, dans les fiches contribuables.

Par ailleurs, pour la taxe d'assainissement qui relève des recettes non fiscales, les insuffisances suivantes ont été notées :

- Une discrimination dans les textes organisant le régime auquel sont soumis les assujettis (régime déclaratif auto liquidatif pour les producteurs et distributeurs des matières plastiques dans la ville de Kinshasa et régime où la taxe fait l'objet de constatation et liquidation pour les activités commerciales, artisanales, industrielles, de grande distribution, des services, des installations portuaires, de déchargement des wagons et unités flottantes, de stockage et d'élevage) ;
- Immunisation de la catégorie des contribuables « ménage » parmi les contribuables ciblés par la taxe, bien que la taxe soit intitulée « Taxe d'assainissement et enlèvement d'immondices ou ordures ménagères » ;
- Modalités de paiement clairement définies par un arrêté conjoint des ministres provinciaux ayant l'environnement et les finances dans leurs attributions pour les uns et non clairement définies comme le veut les textes en la matière.
- L'insuffisance de la contrepartie de la taxe comme service rendu aux redevables. Dans la convention entre la ville province de Kinshasa et la FEC concernant les producteurs et distributeurs des matières plastiques, la province s'engage à organiser un service d'assainissement de la ville mais dans les faits, les services mis en place sont défaillants.

2.2.3 Rendement des actes générateurs (IF, IRL et taxe d'assainissement)

A cet égard ; le diagnostic a révélé :

- Une défaillance dans la mobilisation des recettes des impôts fonciers et des impôts sur les revenus locatifs par rapport au potentiel fiscal de la province dans ce domaine, la perception étant concentrée sur les personnes morales et les grandes personnes physiques (97% pour l'IF et 98% pour l'IRL) ;
- Une défaillance dans la mobilisation des recettes de la taxe d'assainissement par rapport au principe du 'pollueur-payeur', au potentiel fiscal de la ville dans le secteur et aux défis de l'assainissement pour la ville de Kinshasa.

2.2.4 Organisation des registres des services cadastraux et tenue des Plans de lotissement, plans cadastraux, calques

Sur ce chapitre, il a été noté que dans la totalité des circonscriptions foncières, l'organisation des données repose sur une logique essentiellement administrative et fonctionnelle, et non sur une logique fiscale intégrée. Aucune circonscription ne dispose d'un système d'information cadastral numérique structuré, centralisé ou interopérable. Les données sont conservées sous forme de registres manuels, de planches papier, de calques anciens ou de fichiers isolés, sans standard commun ni mécanisme de mise à jour coordonné. En substance, il a été noté les faits ci-après :

- Les plans de lotissement, plans cadastraux et calques existants ne sont ni numérisés ni mis à jour ;
- Absence d'une cartographie fiable pour géolocaliser les biens imposables aux fins de la constitution d'un répertoire automatisé moderne (il s'observe un décalage important entre la cartographie officielle et la configuration réelle des parcelles dans la ville et les plans cartographiques existant dans chaque circonscription sous format manuel ou numérisé ne comportent aucune information liée à la fiscalité) ;
- Les plans cadastraux, obsolètes dans la quasi-totalité, ne reflète plus la réalité du terrain (la mise à jour est rare, souvent inexistante, et les documents datent pour la plupart de l'époque coloniale ou de décennies antérieure et, en cas de mutation, morcellement, conversion, cession ou

construction nouvelle, les informations sont inscrites dans les registres administratifs, mais rarement répercutées sur les plans) ;
- L'inexistence d'un système d'information cadastral numérique, les registres utilisés étant presque exclusivement manuels, disparates et fragmentés selon les bureaux ;
- Les cahiers d'enregistrement existant dans les services, des formats variables, ne suivent aucun standard commun, ce qui limite leur utilisation pour un système intégré.

2.2.5 Organisation du répertoire des contribuables des actes générateurs

L'organisation du répertoire des contribuable, bien qu'informatisée, est partiellement fonctionnelle. Les insuffisances décelées concernent :

- L'inobservance par les contribuables de l'obligation de l'immatriculation /enregistrement pour toutes les opérations entre les contribuables et les services de l'Etat, y compris les Entités Administratives Décentralisées ;
- Le caractère fortement déclaratif des enregistrements ;
- La non-numérisation des dossiers des contribuables ;
- Le Fonctionnement des services en silos sans coordination en matière de gouvernance des données fiscales et d'assurance qualité ;
- Le déficit dans la détection des contribuables non répertoriés (le répertoire ne couvre qu'une fraction marginale du patrimoine foncier taxable trahissant un déficit en matière de recensement, recoupement et recherche) ;
- Les effectifs extrêmement faibles enregistrés par la DGRK en matière d'IF et d'IRL au regard de la réalité foncière de la Ville de Kinshasa (1058 contribuables dont 703 personnes morales pour l'IF, 30202 contribuables dont 2571 personnes morales pour l'IRL et 530 contribuables dont 215 personnes morales pour la RL).
- La limitation du répertoire existant pour la Taxe d'Assainissement essentiellement aux entreprises affiliées à la FEC, en particulier les producteurs et distributeurs de matières plastiques et le non-enregistrement systématique des autres catégories de redevables prévues par les textes légaux, notamment les établissements commerciaux, ménages, opérateurs informels, gestionnaires d'espaces publics ou entreprises génératrices de déchets ;
- L'opacité dans les opérations d'assiette menées par les Directions fiscales ainsi que les Divisions provinciales des affaires foncières et de l'environnement et développement durable ;
- Le sous-recensement massif des propriétaires et des biens bâtis et non bâtis consécutif à l'absence de mécanismes de recensement digital systématique et structuré, l'absence de géolocalisation des parcelles permettant d'associer une unité fiscale à une localisation physique,
- Le manque de collaboration systématique avec les services de collecte des déchets et les communes ;
- Les limites techniques du système e-DGRK, notamment une architecture limitée, non documentée et fragile, due à la déconnexion entre la base d'assiette de la **DGRK** (cadastre fiscal) et le cadastre foncier, absence de passerelle de données qui révèle un problème de partage de l'information structurel et entrave la mise à jour des mutations immobilières ;
- L'absence totale de géolocalisation numérique, lacune qui interdit toute vérification physique externe (VFE) et toute analyse spatiale de l'assiette,
- L'incapacité d'assurer le contrôle d'unicité et la mise à jour automatisée et l'absence d'interopérabilité en vue des rapprochements avec les circonscriptions foncières ainsi que d'autres services disposant d'informations pertinentes pour assurer l'intégrité et l'enrichissement du répertoire des contribuables (DGI, REGIDESO, SNEL, GUCE, notariats communaux, etc.).

En résumé, le logiciel « e-dgrk » est limité à une fonction de registre numérique. Sa conception initiale n'intègre aucune logique prédictive ou de contrôle moderne. Il ne dispose d'aucune intelligence fonctionnelle moderne : absence de moteur de déduplication, d'un module de système d'information.

3. Analyse fonctionnelle du répertoire existant

Le diagnostic du répertoire existant a été réalisé dans un contexte où l'accès aux informations a été partiellement restreint. Toutes les composantes du répertoire n'ont pas pu être consultées dans leurs formats complets. Les experts n'ont pas eu accès à l'ensemble des bases recommandées par le Ministère provincial des Finances.

Cependant, des entretiens approfondis avec les responsables des services en charge :

- De l'identification ;
- De l'enregistrement ;
- De la fiscalisation des contribuables ;

ont permis de reconstituer les principaux processus en vigueur et d'apprécier la fiabilité globale du registre. Faute d'accès intégral aux bases, les informations n'ont pas toujours pu être vérifiées par recoupement avec des sources tierces. Les conclusions présentées ci-après

3.1 Modalités actuelles d'enregistrement des contribuables

L'inscription d'un contribuable dans le répertoire se fait aujourd'hui principalement à partir d'une **fiche d'identification manuelle** remplie par le requérant.

a) Personne morale :

- Raison sociale ;
- Sigle ;
- Numéro d'identification fiscale (NIF) :
- RCCM :
- Numéro d'identification nationale (ID.NAT) :
- Téléphone :
- E-mail :
- Adresse physique (siège) :
- Type d'impôt :
- Valeur :
- Adresse de la propriété :
- Identification du bien :
- Personne à contacter (Noms et signature) :
- Lieu et date d'émission ;
- Signature et seau.

b) Personne Physique :

- Noms :
- Numéro d'identification fiscale (NIF) :
- Téléphone :
- E-mail :
- Adresse physique :
- Type d'impôt :
- Valeur :
- Adresse de la propriété :
- Identification du bien :
- Lieu et date d'émission ;
- Signature et seau.

À noter qu'aucune « demande d'enregistrement » n'est formellement requise du requérant, aucun formulaire n'étant pas prévu à cet effet.

La fenêtre du portail du contribuable sur le site internet de la DGRK qui permettrait aux contribuables de s'enregistrer afin de sa fiscalisation ou de mettre à jour les données contenues dans le répertoire étant fermée temporairement, il a été impossible de vérifier les informations requises en ce qui concerne l'identification du bien tel que prévue dans le système ou la base des données.

Néanmoins, selon les informations recueillies, lors de l'enregistrement du contribuable dans le système, ce dernier permet d'enregistrer i) les types d'impôts et taxes auxquels il est assujetti ; ii) le type de propriétés soumis à l'IF ou à l'IRL.

Pour la taxe d'assainissement, en ce qui concerne le répertoire des contribuables producteurs et distributeurs des matières plastiques dans la ville de Kinshasa, ce dernier ne consiste qu'à une liste de 68 entreprises membres de la FEC. Les seules informations utiles qui y figurent sont la raison sociale, l'adresse, l'activité et l'observation (en activité).

3.2 Logique des titres de propriété

En matière foncière, les seuls titres de propriété ayant force légale sont le contrat de location et le certificat d'enregistrement. La première cité est un titre temporaire décerné au requérant sur base d'une demande de terre et dont la validité est de 3 ans pour les terrains non mis en valeur dans les nouveaux lotissements, tandis que le second est décerné au requérant pour les terrains mis en valeur, accompagné d'un contrat de concession perpétuelle et ce pour une durée indéterminée.

Il va de soi qu'en matière fiscale, la situation évolue du premier stade de « propriété non bâtie » vers le second dit « propriété non bâtie ». Ce dernier comprend une situation très diverse qui est spécifiée dans les textes légaux.

Pour la Ville province de Kinshasa, conformément à l'arrêté du ministre provincial n° 17/CAB/MIN.PROV/FIN.ECO/2023 du 07 décembre 2023 modifiant et complétant l'arrêté n° 007/CAB/MIN.PROV/FIN.ECO/2022 du 30 mars 2022 fixant les taux des impôts sur les superficies des propriétés bâties et non bâties de la ville de Kinshasa, les propriétés bâties soumises à l'IF comprennent :

- Les villas et immeubles autres qu'à étage ;
- Les immeubles à étage ;
- Les appartements ;
- Les autres constructions.

Sont considérées comme autres constructions, notamment :

- Le hangar à usage industriel ou commercial ;
- La toilette avec vestiaires isolés ;
- La guérite ;
- Le citerne ou tank fixé au sol ;
- La piscine ;
- Le local moteur ;
- La station-service ;
- La terrasse ;
- L'entrepôt ;
- Le dépôt ;
- L'émetteur ou le récepteur fixé au sol ;
- Le garage isolé ;
- La station terrienne réceptrice ;
- Le conteneur fixé ou immobilisé au sol ;
- Le parking intérieur aménagé ;
- L'antenne de télécommunication.

Ces autres constructions peuvent exister seules ou coexister avec les autres propriétés foncières premières citées sur un même fond couvert par un seul titre de propriété et donc être mentionnées dans la déclaration de la propriété foncière bâtie seule avec les trois premièrement citées.

Les éléments essentiels contenus dans un titre de propriété, à l'occurrence le certificat d'enregistrement, et rentrant dans les mentions à compléter pour identifier le contribuable et le bien objet d'imposition, sont les suivantes :

a) Pour l'identification du contribuable et du contrat

- Noms :
- Profession :
- Nationalité :
- Lieu et date de naissance :
- N° carte d'identité :
- Lieu et date de délivrance :
- Régime matrimoniale :
- Noms du conjoint :
- Adresse de résidence :
- Références du certificat (Vol et Folio) :
- N° du contrat de concession perpétuelle :
- Date de conclusion :
- N° d'ordre général du registre journal :
- N° d'ordre spécial :
- Lieu et date d'émission ;
- Signature et seau.

b) Pour l'identification du bien

- Adresse physique de la propriété :
- N° SU du plan cadastral communal :
- Superficie :
- N° du PV de mesurage et bornage :
- Date d'établissement du PV :
- Nature et usage des ouvrages bâtis sur le terrain :

Il y a lieu de retenir que pour l'identification correcte du bien soumis à l'imposition, l'adresse physique de la propriété doit spécifier le quartier, étant donné que dans une même commune peut coexister des quartiers relevant des différents rangs correspondant à différents tarifs fiscaux.

3.3 Règles d'identification du contribuable

À part l'obligation d'immatriculation /enregistrement faite à tout contribuable pour toutes les opérations entre les contribuables et les services de l'Etat, pour la ville province de Kinshasa, il n'existe aucun protocole de quelque forme que ce soit (sous forme de circulaire ou d'instruction) fixant les règles d'identification du contribuable.

Contrairement aux pratiques en vigueur dans d'autres services publics comme le GUCE dans le cadre de l'assainissement du climat des affaires, cette carence est préjudiciable aux contribuables qui n'ont pas ainsi accès à l'information sur les éléments constitutifs du dossier d'identification aux fins de son enregistrement dans le répertoire des contribuables à l'IF, l'IRL ainsi que les autres impositions de nature quelconque.

3.4 Cohérence avec IF, IRL, TAS

En principe, l'IF, l'IRL et la taxe d'assainissement reposent tous les trois sur un même fond, bien que leurs faits générateurs soient différents. En effet, c'est sur une même propriété foncière que se réalisent les transactions de bail et l'assainissement et enlèvement des immondices.

De ce fait, en ce qui concerna la fiscalité, les trois actes étant dans la plupart des cas liés, l'élaboration d'un répertoire des contribuables devra tenir compte de cette articulation.

Le lien de fond entre l'IRL et l'IF est tellement clair et indiscutable que cela ne demande pas une démonstration. Quant à la taxe d'assainissement, bien qu'elle soit liée à une propriété foncière en location ou pas, le locataire qui est le redevable de la retenue locative l'est aussi pour la taxe d'assainissement. Il y a ainsi lieu de mutualiser le paiement de ces deux actes qui, dans la plupart de cas, ont une même périodicité pour cette catégorie de contribuables. Si cela est faisable pour certains redevables de la catégorie des personnes physiques exerçant une activité économique, artisanale, industrielle ou de service, cela n'est pas évident pour la catégorie des ménages tant qu'il n'y aura pas de contrepartie de la part de la ville en termes d'enlèvement d'immondices ou ordures ménagères.

3.5 Nomenclatures de l'IF, l'IRL et de la TAS et dispositions applicables

Il convient de noter que pour chaque acte générateur, il y a des catégorisations auxquelles correspondent différents tarifs fiscaux. Cette discrimination doit être mis en évidence dans l'architecture de la configuration des registres des contribuables à chaque type d'impôt ou taxation au sein du système informatique de l'administration fiscale.

3.5.1 Impôt sur les propriétés foncières bâties et non bâties

Les paramètres de tarification de l'IF se basent sur deux facteurs : les propriétés foncières bâties et les propriétés foncières non bâties d'une part et le rang de localisation de la propriété (classification qui va du 1er au 4ème rang).

Pour les propriétés foncières bâties, la nomenclature retient 4 types de propriétés :

- Les villas et immeubles autres qu'à étage ;
- Les immeubles à étage ;
- Les appartements ;
- Les autres constructions

Pour les immeubles en étages, une discrimination est faite entre :

- Immeuble à étage appartenant à un seul propriétaire ou à une indivision et
- Immeuble à étage appartenant à plusieurs propriétaires.

Pour les propriétés foncières non bâties, il est retenu une tarification progressive à deux tranches ou paliers :

- Premier palier (de 1 à 5000 m2) et
- Deuxième palier (de 5001 à plus).

Dans tous les cas, les propriétaires sont classifiés en trois catégories :

- Les personnes morales autres que les sociétés immobilières ;
- Les sociétés immobilières ;
- Les personnes physiques.

La tarification établie par l'arrêté du ministre provincial n° 17/CAB/MIN.PROV/FIN. ECO/2023 du 07 décembre 2023 précité consacre une facturation au M^2 pour les personnes morales et une facturation forfaitaire pour les personnes physiques.

Dans les deux cas de fifure, la situation se présente comme suit :

PROPRIETES FONCIERES BATIES												
Rang	Villas et Immeubles autres qu'à étages			Immeubles autres qu'à étages			Immeubles autres qu'à étages			Appartements		
	P.M. autres	S. Immob.	P. Phys.	P.M. autres	S. Immob.	P. Phys.	P.M. autres	S. Immob.	P. Phys.	P.M. autres	S. Immob.	P. Phys.
1er Rang												
2ème Rang												
3ème Rang												
4ème Rang												

Rang	Tranche	Autres constructions			PROPRIETES FONCIERES NON BATIES		
		P.M. autres	S. Immob.	P. Phys.	P.M. autres	S. Immob.	P. Phys.
1er Rang	1 à 500 m^2						
	500 m^2 et +						
2ème Rang	1 à 500 m^2						
	500 m^2 et +						
3ème Rang	1 à 500 m^2						
	500 m^2 et +						
4ème Rang	1 à 500 m^2						
	500 m^2 et +						

***P.M. :** Personne Morale ; S. Immob. : Société Immobilière ; P. Phys. : Personne physique.

3.5.2 Impôt sur les revenus locatifs

Pour l'IRL, les paramètres de tarification sont fixés sur base des éléments ci-après :

- Le revenu brut des bâtiments et terrains ;
- Le profit brut de la sous-location totale ou partielle des mêmes propriétés ;
- Les indemnités de logement accordées à des rémunérés occupant leurs habitations ou celle de leurs époux(ses) ;
- Les indemnités de logement accordées à des rémunérés occupant les habitations appartenant à des tiers à titre gratuit ;
- La mise à disposition, à titre gratuit, des bâtiments et terrains en faveur d'une entreprise ou de toute autre personne pour usage professionnel.

Pour les revenus bruts des bâtiments et terrains ainsi que les profits, les taux de l'IRL et la retenue sur loyer (RL) sont fixés en pourcentage suivant le rang de la localité.

Rang de localité	Loyer mensuel	Taux IRL	Taux R.L
1er Rang	Loyer ou profit brut	22%	20%
2ème à 4ème rang	Loyer ou profit brut	17%	15%

Pour les indemnités de logement accordées à des rémunérés occupant leurs habitations ou celle de leurs époux(ses) :

Catégorie	Indemnité de logement	Taux IRL
1er	Indemnités de 301$ et plus	22%
2ème	Indemnités de 1$ à 300$	17%

Pour les bâtiments et terrains mis à disposition, à titre gratuit, en faveur d'une entreprise ou de toute autre personne pour usage professionnel.

Rang de localité	Taux mensuel forfaitaire/m^2 en $
1er rang	20
2ème rang	15
4ème rang	10
4ème rang	5

3.5.3 Taxe d'assainissement

La législation provinciale ne fiscalise que deux catégories des contribuables :

- Les entités (entreprises) productrices ou distributrices des matières plastiques et
- Les personnes physiques ou morales exerçant une activité économique artisanale, industrielle et de service dans la ville de Kinshasa.

Pour les entités productrices ou distributrices des matières plastique, les assujettis sont catégorisés en 10 groupes à savoir :

Catégorie	Rang	Montant ($)
Catégorie A1	Grandes entreprises productrices des PET	4000
Catégorie A2	Petites entreprises productrices des PET	2000
Catégorie B	Entreprises productrices des emballages en plastique autres que les PET	2000
Catégorie C	Entreprises productrices des plastiques autres que les emballages	2000
Catégorie D	Entreprises utilisatrices des PET comme emballages	2000
Catégorie E	Entreprises conditionnant les produits cosmétiques dans des emballages plastiques	2000
Catégorie Fa	Grandes entreprises distributrices des produits plastiques	2000
Catégorie Fb	Moyennes entreprises distributrices des produits plastiques	1500
Catégorie Fc	Petites entreprises distributrices des produits plastiques	750
Catégorie G	Entreprises conditionnant les produits pharmaceutiques dans des emballages plastiques	500

Pour les personnes physiques ou morales exerçant une activité économique artisanale, industrielle et de service, elles sont catégorisées en 17 groupes, non compris les activités d'élevage et installations foraines, dont chaque composante a un taux spécifique. Il s'agit de :

- Entreprises tabacoles ;
- Entreprises de panification ;
- Autres sociétés de production ;
- Autres industries de transformation ;
- Industrie alimentaire ;
- Industrie métallique ;
- Mise en forme ;
- Société de construction ;
- Industrie du bois ;
- Industrie pétrolière et produits assimilés ;
- Entreprises de prestation et de service industrielle, hôtellerie et récréative ;
- Communication ;
- Société de transport ;
- Banques et institution financières ;
- Produits manufacturés ;
- Médico-sanitaires ;
- Établissements publics et d'utilité publique.

Comme on peut le constater, cette catégorisation demande une harmonisation dès lors que dans l'annexe à l'arrêté on parle de sociétés alors qu'il s'agit des personnes physiques ou morales exerçant une activité économique artisanale, industrielle et de service.

Par ailleurs, le principe de base étant celui du « pollueur-payeur », les activités marchandes productrices des immondices et déchets dans les marchés central et communaux et dont la gestion est structurée (présence d'un comité du marché et d'un administrateur) devraient être prise en compte dans cette nomenclature, étant donné que c'est là la principale source des déchets solides produits par les ménages. Des règles applicables en matière d'assiette, il y a lieu de rappeler les dispositions de l'Edit n° 005/2021 du 25 décembre 2021 précitée et des arrêtés fixant les taux de la taxe d'assainissement.

3.5.4 Impôt foncier

Article 17. L'assujetti à l'impôt sur la superficie des propriétaires bâties ou non bâties est tenu chaque année d'en souscrire une déclaration au plus tard le 1er février.
Article 19. En cas de mutation d'une propriété par suite de vente ou de toute autre cause, le nouveau propriétaire est tenu d'en faire la déclaration dans un délai d'un mois prenant cours la date de ladite mutation.

3.5.5 Impôt sur les revenus locatifs

Article 28. L'assujetti à l'impôt sur les revenus locatifs est tenu chaque année d'en souscrire une déclaration au plus tard le 1er février de l'année qui suit celle de la réalisation des revenus.
Article 31. Le redevable légal de la retenue à la source de l'impôt sur les revenus locatifs est tenu de souscrire sa déclaration….
Article 30. Les personnes physiques ou morales assujetties à l'impôt sur les revenus locatifs sont tenues de joindre à leurs déclarations un état précisant pour chaque propriété :

- La nature ;
- L'adresse (commune, rue, n°) ;
- L'affectation (jouissance personnelle, location à titre onéreux, mise à disposition à titre gratuit, etc.) ;
- La désignation complète du ou des occupants avec pour chacun d'eux :
  - La destination de l'immeuble ou de la portion de l'immeuble occupé (logement, commerce, industrie, etc.) ;
  - Le montant du loyer ;
  - La superficie développée de la partie bâtie.

Toutefois, la retenue du loyer de 20% effectuée par le locataire est versée dans les dix jours qui suivent celui du paiement du loyer à l'aide d'un modèle fixé par le DGRK.

3.5.6 Taxe d'assainissement

Selon les dispositions règlementaires, le paiement de la taxe est mensuel et exigible au plus tard le 10ème jour du mois.

Pour les producteurs et distributeurs des produits plastiques, le paiement est auto-liquidatif. Pour les personnes physiques ou morales exerçant une activité économique artisanale, industrielle et de service, le paiement est à constatation et ordonnancement préalable par le service d'assiette, à l'occurrence la Division provinciale de l'Environnement et Développement durable.

4. Analyse technique du répertoire existant

Cette section décrit l'état technique réel du dispositif d'administration de l'assiette des IF, IRL et TAS. Elle couvre la base de données, l'architecture applicative, les interfaces avec les systèmes externes, les processus d'alimentation, le niveau d'automatisation et les principales contraintes d'infrastructure, d'outillage et de sécurité. Elle met en évidence les limites structurelles qui rendent nécessaire la mise en place d'un nouveau système de type SIGREC.

4.1 Base de données et architecture existantes

L'analyse menée montre qu'il n'existe pas aujourd'hui de **système de gestion centralisé** dédié à l'assiette des IF, IRL et TAS. Le dispositif en place se présente plutôt comme une mosaïque d'outils et de fichiers, sans véritable architecture unifiée.

Les éléments suivants ressortent :

- le système « e-DGRK » repose sur une architecture proche du monolithe applicatif, construite autour d'une base de données relationnelle classique ;
- pour l'assiette, une partie importante des informations reste gérée dans des fichiers Excel ou Access, au niveau des services et unités internes ;
- il n'existe pas de base de données centralisée et unique pour l'ensemble des contribuables et des biens, ce qui entraîne la création de multiples versions parallèles ;
- le modèle de données n'est pas documenté, il n'y a ni dictionnaire de données ni schéma conceptuel ou logique formalisé ;
- les champs existants ne permettent pas de porter une identification foncière moderne, car manquent notamment un identifiant unique robuste, les coordonnées géographiques, le statut foncier détaillé et l'historique des mutations.

Sur le plan technique, le dispositif ressemble davantage à un **référentiel administratif partiellement numérisé** qu'à un système d'information structuré. L'absence de véritable SGBD transactionnel bien administré, avec contraintes d'intégrité et règles de gestion explicites, empêche d'assurer :

- la cohérence interne des données ;
- la traçabilité des modifications ;
- la montée en charge vers un registre fiscal exhaustif.

Enfin, la base actuelle n'est pas adaptée au stockage de **données spatiales**. Elle ne dispose ni de champs géométriques ni de mécanismes de gestion cartographique. Cela limite fortement toute capacité d'analyse géographique de l'assiette et rend impossible, en l'état, l'intégration d'un module SIG performant.

4.2 Fragmentation des données et absence de centralisation

Le répertoire des contribuables n'est pas géré comme une base unique, mais comme un ensemble de listes et de fichiers dispersés.

On observe notamment :

- des fichiers distincts par service ou par impôt, sans mécanisme de consolidation automatique ;
- des bases locales construites au fil des années selon les besoins opérationnels, sans standard commun ni nomenclature harmonisée ;
- des dossiers techniques et titres fonciers conservés physiquement dans les treize circonscriptions foncières, sans indexation numérique systématique.

Cette fragmentation produit plusieurs effets :

- doublons nombreux pour un même contribuable ou un même bien ;
- incohérences entre différents fichiers pour une même information ;
- impossibilité de retracer l'historique des mises à jour et corrections ;
- difficulté à produire des états de synthèse fiables pour la décision.

En l'absence de serveur central dédié au répertoire et de base de données unique, l'administration ne dispose pas d'une vision consolidée et actualisée de l'assiette fiscale sur l'ensemble de la ville.

4.3 Interfaces, sources de données et processus d'alimentation

4.3.1 Interfaces inexistantes ou très limitées

Le système actuel fonctionne de manière fermée. Il ne dialogue pas de façon structurée avec les autres producteurs de données pertinentes, en particulier :

- les circonscriptions foncières (cadastre, conservation) ;
- les services d'urbanisme et de l'habitat ;
- les notariats communaux ;
- la DGI (pour les NIF et autres données fiscales nationales) ;
- la SNEL et la REGIDESO (pour les points de fourniture d'électricité et d'eau) ;
- le GUCE (pour les créations et modifications d'entreprises).

Aucun connecteur, aucune API ni protocole d'échanges automatisés n'est en place. Les échanges de données, lorsqu'ils existent, se font par transmission ponctuelle de fichiers ou par consultation manuelle de registres physiques.

Cette absence d'interface technique empêche :

- la vérification systématique des titres de propriété ;
- le suivi en continu des mutations foncières et des opérations immobilières ;
- l'actualisation régulière des coordonnées et caractéristiques des biens ;
- la détection croisée des incohérences entre bases.

4.3.2 Sources de données actuellement utilisées

Les sources de données potentiellement mobilisables sont nombreuses, mais sous exploitées :

- **circonscriptions foncières** pour les informations parcellaires et les certificats d'enregistrement ;
- **divisions de l'habitat** et notariats pour les baux et contrats de location (IRL) ;
- **DGI** pour les NIF, les déclarations fiscales nationales et certains indicateurs d'activité ;
- **SNEL** et **REGIDESO** pour l'identification des unités occupées et des consommateurs ;
- **GUCE** pour les entreprises nouvelles, mutées ou radiées.

En pratique, ces sources sont consultées de manière ponctuelle, souvent sous forme papier ou de fichiers isolés, sans intégration dans un flux numérique continu.

4.3.3 Processus d'alimentation du répertoire

L'alimentation du répertoire se fait aujourd'hui selon un schéma largement manuel :

1. collecte d'informations sur le terrain ou auprès de services partenaires ;
2. transmission sous forme de listes papier ou de fichiers simples ;
3. saisie manuelle par les agents dans des fichiers ou bases non centralisés ;
4. absence de validation automatique des champs critiques ;
5. absence de rapprochement systématique avec les sources externes.

Ce mode de fonctionnement entraîne :

- lenteur dans la mise à jour du répertoire ;
- forte dépendance à la disponibilité et au niveau de formation des agents ;
- risque élevé d'erreurs de saisie, d'omissions et de divergences ;
- impossibilité d'auditer de manière fiable le processus de constitution de l'assiette.

4.3.4 Niveau d'automatisation actuel

Le niveau d'automatisation du dispositif est très faible au regard des standards actuels de l'administration fiscale.

Les fonctions observées se limitent à :

- quelques calculs automatiques de montants d'impôt, une fois les données saisies

- génération de certains titres de perception ou documents de notification
- éventuelles extractions ponctuelles pour des besoins statistiques limités

En revanche, le système ne propose aucune automatisation pour des fonctions clés comme :
- la **création d'un identifiant unique** de contribuable ou de parcelle (NIF, identifiant foncier) ;
- le **contrôle de complétude** des fiches d'enregistrement ;
- la **détection des doublons** entre fichiers ou entre services ;
- la mise à jour automatique en fonction d'événements externes (mutation foncière, changement d'activité, mise en service d'un compteur, etc.) ;
- la **géolocalisation** des biens et contribuables via des outils de collecte mobile.

Il n'existe pas de workflow automatisé pour l'enregistrement, la validation et la mise à jour d'un contribuable ou d'un bien imposable. Chaque étape dépend d'initiatives individuelles et de pratiques locales, ce qui rend la qualité des données très variable d'un service à l'autre.

4.3.5 Contraintes d'infrastructure et d'outillage

4.3.5.1 Infrastructure matérielle et réseau

Les contraintes liées à l'infrastructure sont importantes :
- absence de serveur central spécialement dédié au répertoire des contribuables ;
- limitations matérielles dans les divisions et circonscriptions, avec un nombre réduit de postes de travail et des équipements vétustes ;
- réseau interne incomplet, voire inexistant, entre certains services, ce qui empêche la remontée des données en temps réel.

Cette situation rend difficile :
- la mise en place d'un système multi-utilisateurs fiable ;
- la gestion centralisée des accès et des droits ;
- la synchronisation des données entre terrain et niveau central.

4.3.5.2 Alimentation électrique

La fiabilité logistique est également un problème majeur :
- alimentation électrique instable ;
- insuffisance d'onduleurs et de groupes électrogènes ;
- risques de coupures en cours de saisie ou de traitement.

Ces faiblesses augmentent le risque de perte de données et diminuent la disponibilité du système. Elles sont incompatibles avec l'exploitation d'un système d'information critique pour les recettes.

4.3.5.3 Outils logiciels

Les outils utilisés sont essentiellement :
- fichiers Excel et bases Access, qui ne sont pas conçus pour gérer des volumes importants de données ni pour assurer une multi-utilisation sécurisée ;
- quelques modules applicatifs non intégrés, développés sans schéma d'urbanisation global.

Ces outils souffrent de plusieurs limites :
- instabilité et risques de corruption de fichiers ;
- absence de mécanismes de sauvegarde automatique et de restauration ;
- pas de gestion de versions ni de journalisation des modifications.

4.3.6 Sécurité, droits d'accès et gouvernance technique

Sur le plan de la sécurité, les constats sont également préoccupants.
On note notamment :
- absence de gestion fine des profils et des rôles ;
- pas de politique formalisée de gestion des mots de passe et des comptes utilisateurs ;
- absence de chiffrement des données sensibles en base ou en transit ;
- inexistence de piste d'audit permettant de suivre qui a fait quoi, quand et sur quel enregistrement.

Ces lacunes augmentent les risques :

- de manipulation non autorisée des données ;
- de divulgation d'informations confidentielles ;
- de contestation de la fiabilité des données fiscales.

Elles vont à l'encontre des exigences minimales attendues pour un système d'information fiscal gérant des données nominatives et patrimoniales sensibles.

4.3.7 Contraintes méthodologiques et organisationnelles liées au volet technique

Les difficultés techniques sont renforcées par plusieurs limites méthodologiques :

- absence de **modèle conceptuel de données** validé ;
- manque de documentation technique décrivant le fonctionnement du système actuel et les flux de données ;
- inexistence de normes communes pour la saisie des adresses, la typologie des biens, les catégories de contribuables ou les codes d'activité ;
- hétérogénéité des pratiques d'un service à l'autre, faute de référentiel partagé.

Ces éléments compliquent :

- toute tentative d'unification des fichiers existants ;
- la définition d'un modèle cible clair ;
- la migration vers une nouvelle base de données sans perte ni déformation d'information.

Ils montrent aussi que la réforme technique devra être accompagnée d'une **clarification organisationnelle** et d'un effort de normalisation des procédures et des formats de données.

Tableau 2: Synthèse des principaux constats techniques

Domaine	Constats principaux	Conséquences pour le projet SIGREC
Architecture et base de données	Dispositif fragmenté, absence de base centralisée, modèle non documenté, pas de gestion des données spatiales	Nécessité de concevoir une base centralisée, spatiale, normalisée et documentée
Centralisation des données	Multiplicité de fichiers locaux, absence d'historique fiable, incohérences fréquentes	Travail important d'assainissement et de consolidation avant migration
Interfaces et échanges	Aucune API ni connecteur avec cadastre, DGI, SNEL, REGIDESO, GUCE, Habitat	Mise en place indispensable d'interfaces techniques et de protocoles d'échange de données
Processus d'alimentation	Collecte et saisie entièrement manuelles, lenteur, erreurs fréquentes, absence de recoupement	Conception de processus d'alimentation hybrides terrain/central, appuyés sur des outils numériques
Automatisation	Automatisation très limitée, pas de workflow, pas de détection de doublons ni de contrôles automatisés	Implémentation de workflows complets et de contrôles d'intégrité à chaque étape du cycle de vie des données
Infrastructure et logistique	Manque de serveurs, réseau incomplet, alimentation électrique instable	Intégrer un volet infrastructure et énergie dans le projet, comme prérequis technique
Outils et sécurité	Usage massif d'Excel/Access, absence de sauvegarde structurée, pas de gestion des droits ni d'audit	Déploiement d'un SGBD sécurisé, avec gestion des profils, journalisation et plan de reprise après sinistre
Méthodologie et normalisation	Pas de référentiel de données, pratiques hétérogènes, documentation lacunaire	Élaboration d'un modèle de données de référence et de normes de saisie, accompagnées par de la formation

5. Proposition de conception fonctionnelle du répertoire cible (SIGREC)

Le futur SIGREC doit être conçu comme un **Système d'Information Géographique Fiscal intégré**, dans lequel l'information fiscale (contribuables, impôts, taxes) est articulée en permanence avec l'information spatiale (parcelles, bâtiments, unités locatives, activités).

Le système cible remplace une logique centrée sur le contribuable déclarant par une logique centrée sur **l'objet imposable** (parcelle, bâtiment, activité), qui constitue la base réelle de l'assiette fiscale.

Ainsi, la parcelle devient le **pivot unique** autour duquel se rattachent :

- le propriétaire et/ou l'occupant ;
- les unités locatives ;
- les activités économiques ;
- les impositions IF, IRL et TAS.

L'objectif principal est de disposer d'un répertoire **exhaustif, géolocalisé, mis à jour en continu et juridiquement fiable**.

5.1 Nouveau contenu des fichiers d'identification parcellaires

Le fichier d'identification du système cible est d'abord parcellaire, ensuite nominatif. Autrement dit, le point d'entrée n'est plus la personne qui se déclare, mais l'objet physique imposable, c'est-à-dire la parcelle et les constructions qui s'y trouvent. Cette évolution conceptuelle est essentielle, car elle permet d'ancrer l'assiette fiscale sur des éléments matériels observables, vérifiables sur le terrain et géolocalisables, indépendamment des changements de propriétaires, d'occupants ou d'activités.

Le répertoire ne se limite donc plus à une liste de contribuables. Il devient un **référentiel des parcelles et des biens bâtis**, auquel sont rattachées ensuite toutes les informations fiscales, administratives et juridiques. Ce choix permet d'éviter la disparition d'objets imposables lorsque le propriétaire change ou lorsqu'une déclaration n'est pas réalisée.

5.1.1 Principes

La conception fonctionnelle repose sur trois principes simples et hiérarchisés.

a) On part de l'objet physique : la parcelle

La parcelle constitue l'unité de base de la fiscalité foncière. Elle existe indépendamment:

- du propriétaire ;
- du locataire ;
- de l'activité exercée ;
- des mutations juridiques.

Elle peut être observée, mesurée, cartographiée et décrite. En partant de la parcelle, le système cible garantit que **tout ce qui existe physiquement sur le territoire est potentiellement intégré dans l'assiette**, y compris lorsque le contribuable n'a pas effectué de démarche déclarative.

***b)* On y associe les bâtiments et les unités**

Une même parcelle peut contenir :

- une maison individuelle (Villa) ;
- un immeuble à plusieurs étages ;
- un ensemble d'appartement ou pièces ;
- un entrepôt ou une usine ;
- des constructions annexes (garage, piscine) ;
- une superficie non bâtie (terrain).

Le système distingue donc clairement :

- la **parcelle ;**
- le **bâtiment ;**
- l'**unité locative** ou d'activité (appartement, magasin, bureau, atelier, stand, etc.).

Cela permet notamment :

- de gérer les immeubles à plusieurs unités ;
- d'identifier les logements loués et ceux occupés par le propriétaire ;
- de relier plusieurs activités à une même parcelle.

c) On rattache ensuite le ou les redevables

Ce n'est qu'ensuite que sont associés :

- le ou les propriétaires successifs ;
- les locataires commerciaux ou résidentiels ;
- les exploitants d'activités.

Ainsi, si le propriétaire change, la parcelle reste la même avec son historique et ses caractéristiques. Le système ne perd ni l'assiette ni les informations précédentes.

5.1.2 Identification complète de la parcelle

Chaque parcelle doit être identifiée de manière univoque et vérifiable grâce à quatre ***famille**s d'informations complémentaires.*

a) Coordonnées GPS précises

Chaque parcelle reçoit un point géographique (ou plusieurs pour un polygone). Cela permet :

- la localisation exacte sur le terrain ;
- le contrôle par géolocalisation via smartphone ;
- la comparaison avec des images satellites.

b) Géométrie (polygone sur carte)

La géométrie représente :

- la forme réelle ;
- les limites ;
- la superficie calculée.

Elle permet de :

- détecter des empiètements ;
- mesurer automatiquement les surfaces imposables ;
- analyser les zones urbaines en densification.

c) Références cadastrales officielles

Ces références assurent la liaison avec :

- le certificat d'enregistrement ;
- le plan cadastral ;
- les archives foncières ;

Ce lien juridique sécurise la taxation et réduit les contestations.

d) Adresse normalisée

L'adresse est structurée selon une nomenclature standard :

- commune ;
- quartier ;
- avenue/rue ;
- numéro de parcelle ou bâtiment.

La normalisation évite :

- la multiplication d'écritures différentes pour une même adresse

- les confusions entre homonymies
- la perte d'informations pour cause de saisie approximative

5.1.3 Parcelle comme enregistrement unique de référence

Avec ces éléments, chaque parcelle devient un **enregistrement unique** dans le répertoire. À cet enregistrement sont attachés dynamiquement :

- un ou plusieurs propriétaires successifs
- des occupants actuels et passés
- des activités économiques existantes ou historiques
- des unités locatives distinctes
- tous les impôts et taxes qui y sont liés (IF, IRL, TAS)

Le système n'efface donc plus l'histoire.

Il constitue une **trajectoire fiscale et foncière** pour chaque parcelle.

5.1.4 Effets attendus de cette approche

cette approche permet concrètement d'éliminer :

- **les doublons :** une même parcelle ne peut plus être enregistrée sous plusieurs identités différentes
- **les fausses adresses :** seule une adresse géolocalisée et standardisée est valide dans le système
- **les déclarations fictives :** toute déclaration sans correspondant spatial devient suspecte et contrôlable

Elle permet également de :

- détecter facilement les biens non déclarés
- repérer les constructions nouvelles
- suivre l'évolution du bâti dans le temps
- mieux cibler les contrôles fiscaux

En résumé, le fichier d'identification parcellaire devient **la pierre angulaire de la sécurisation de l'assiette**, car tout le reste du système (contribuables, activités, loyers, taxes) vient s'y rattacher de manière structurée.

5.2 Urbanisation du système SIGREC cible

Le schéma d'urbanisation présente l'organisation métier et fonctionnelle du SIGREC sous forme de blocs cohérents reliés entre eux par des flux d'information. Dans la partie supérieure figurent les canaux d'entrée des données, qui correspondent aux différents modes d'enrôlement et de collecte de l'information : recensement mobile réalisé par les équipes terrain, portail en ligne destiné aux contribuables et guichets de la DGRK pour la saisie assistée. Ces canaux permettent d'alimenter le système aussi bien lors des opérations de recensement que tout au long de la vie du répertoire.

Au centre du schéma se trouve le cœur du système, composé des référentiels métiers. On distingue le référentiel parcellaire, le référentiel des contribuables et le référentiel des unités et activités. Ce sont eux qui constituent la base unique et consolidée de données sur laquelle reposent toutes les fonctions fiscales. À partir de ces référentiels s'adossent les trois modules d'assiette ciblés : l'impôt foncier (IF), l'impôt sur les revenus locatifs (IRL) et la taxe d'assainissement (TAS). Chacun applique ses propres règles de gestion tout en partageant les mêmes objets de référence, ce qui garantit la cohérence et l'unicité de l'information. Dans la partie inférieure figurent les modules de contrôle, de pilotage et de cartographie. Ils transforment les données en outils opérationnels : programmation des contrôles, suivi des performances, génération de tableaux de bord et analyses spatiales via le SIG. Ils permettent aux gestionnaires d'orienter les décisions et de cibler les actions de recouvrement et de vérification.

Enfin, sur les côtés du schéma apparaissent les partenaires institutionnels interconnectés avec le SIGREC : cadastre foncier, services d'urbanisme et d'habitat, notaires, DGI pour le NIF, SNEL, REGIDESO, GUCE et autres administrations sectorielles. Les échanges d'information avec ces acteurs alimentent le répertoire

en événements clés (mutations, permis, raccordements, création d'entreprises) et renforcent la fiabilité juridique et technique des données.

Ainsi, le schéma montre un système organisé en couches : la collecte alimente le cœur parcellaire et fiscal, qui à son tour alimente les fonctions de pilotage, tandis que les partenaires externes assurent une actualisation continue et sécurisée des informations. L'urbanisation garantit donc un SIGREC structuré, évolutif et débarrassé des silos, au service d'une gestion moderne et intégrée de l'assiette fiscale locale.

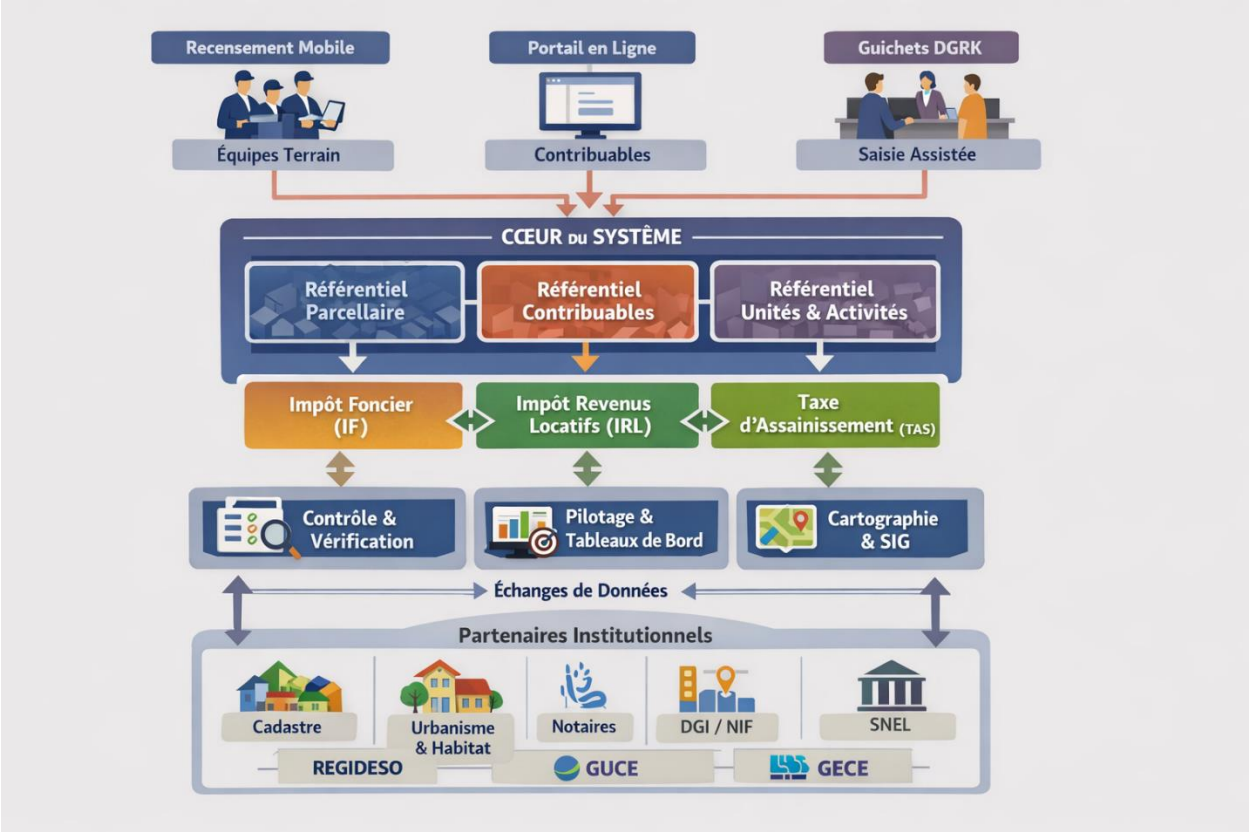

Figure 1 : Urbanisation du système SIGREC cible

5.3 Schéma fonctionnel

Le schéma fonctionnel du SIGREC décrit l'enchaînement logique des principales fonctions du système cible, depuis la constitution des référentiels de base jusqu'aux processus de décision et de pilotage. Il illustre comment les différentes composantes opérationnelles interagissent entre elles pour assurer une gestion complète et cohérente de l'assiette fiscale liée à l'impôt foncier (IF), à l'impôt sur les revenus locatifs (IRL) et à la taxe d'assainissement (TAS).

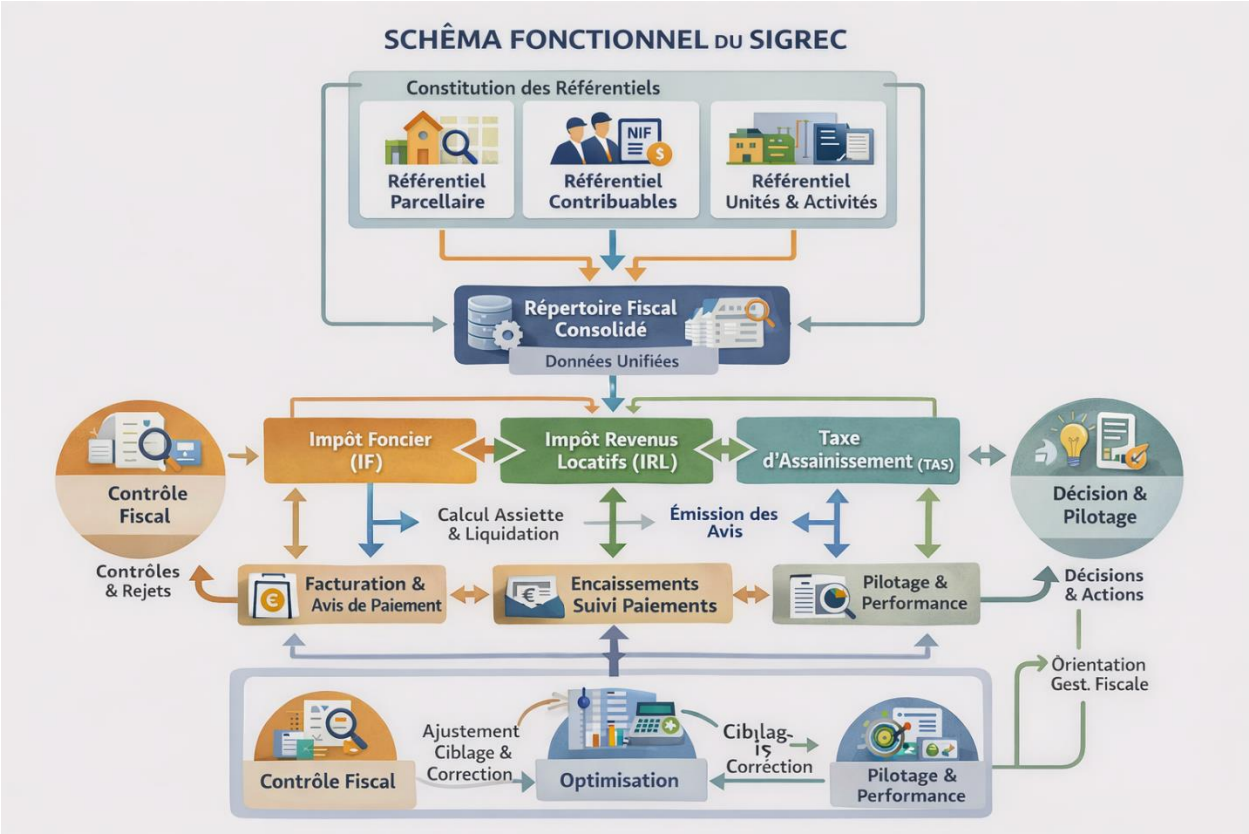

Figure 2 : Schéma fonctionnel du système cible

5.4 Architecture applicative

L'architecture applicative détaillée du SIGREC présente la structuration complète du système cible, en décrivant ses principaux modules applicatifs, leurs rôles respectifs et les échanges d'information qui assurent la cohérence d'ensemble. Elle met en évidence un socle de référentiels uniques (parcelles, bâtiments, unités, contribuables) sur lequel s'appuient les fonctions fiscales, depuis l'enrôlement et la validation des données jusqu'à la détermination de l'assiette, le calcul et la liquidation, l'émission des titres et le recouvrement. Cette architecture intègre également les fonctions transversales indispensables à la fiabilité du dispositif, notamment la gestion des droits et exonérations, le traitement des mutations foncières, le contrôle et l'inspection terrain, ainsi que le reporting, la cartographie SIG et l'aide à la décision. Elle vise ainsi à garantir un système cohérent, évolutif et interopérable, capable de sécuriser la donnée fiscale, de renforcer la traçabilité des opérations et de soutenir un pilotage moderne de l'assiette et des recettes locales.

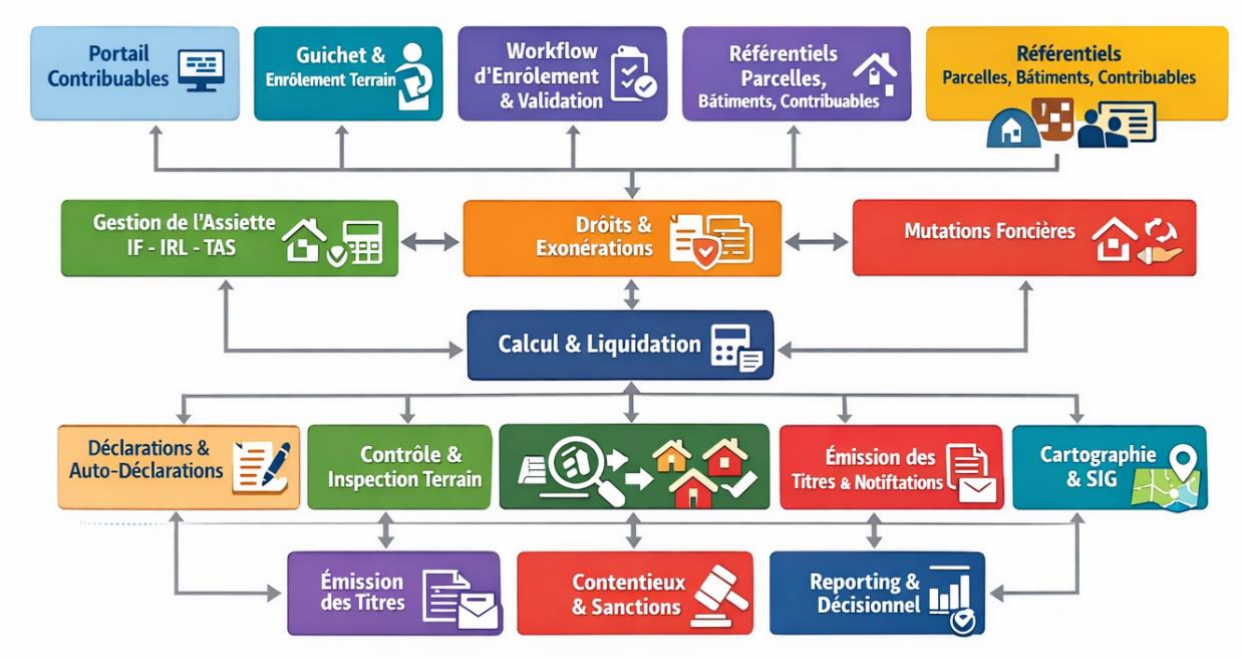

Figure 3 : Architecture applicative

5.4.1 Module de gestion des référentiels (parcelles, bâtiments, unités, contribuables)

Ce module constitue le socle du SIGREC. Il assure la création, la mise à jour et la gestion de l'ensemble des référentiels structurants : parcelles, bâtiments, unités locatives et contribuables. Il garantit l'unicité des identifiants, la cohérence des informations et la géolocalisation des objets fiscaux. Ce module permet également de gérer les liens entre une parcelle, les constructions qui y sont implantées, les activités qui y sont exercées et les redevables qui y sont associés. Il joue un rôle central, car toutes les fonctions fiscales du système en dépendent directement. Sans un référentiel fiable, aucune assiette ne peut être correctement déterminée.

Fonctions principales du module

Les principales fonctions assurées par ce module sont les suivantes :

- création et enregistrement des **parcelles** avec identifiant foncier unique ;
- enregistrement des **bâtiments** et constructions implantées sur la parcelle ;
- gestion des **unités locatives** (appartements, magasins, bureaux, ateliers, etc.) ;
- enregistrement et mise à jour des **contribuables et redevables** (personnes physiques et morales)
- géolocalisation des objets fiscaux par coordonnées GPS et polygones ;
- rattachement d'une parcelle à une adresse normalisée (commune, quartier, avenue, numéro)
- gestion des liens entre :
  - parcelle ↔ bâtiment ↔ unité ↔ activité
  - parcelle ↔ propriétaire ↔ occupant
- conservation de l'historique des modifications (propriétaire, usage, surfaces, statuts) ;
- gestion des statuts des objets : actif, inactif, litigieux, en chantier, démoli ;
- validation et verrouillage des données après contrôle ;
- consultation cartographique et alphanumérique des référentiels.

Ce module constitue ainsi le registre de référence utilisé par tous les autres modules (assiette, contrôle, liquidation, contentieux).

Règles de gestion associées

Le module applique un ensemble de règles de gestion destinées à garantir la fiabilité du référentiel :

- une parcelle correspond à un identifiant foncier unique, qui ne peut jamais être réattribué ;
- un contribuable correspond à un NIF unique, utilisé comme identifiant fiscal principal ;

- une parcelle peut comporter un ou plusieurs bâtiments ;
- un bâtiment peut comporter une ou plusieurs unités locatives ;
- une unité locative est toujours rattachée à une seule parcelle ;
- un contribuable peut être lié à plusieurs parcelles (multi-propriétés) ;
- chaque changement de propriétaire crée un historique, sans effacer l'ancien titulaire ;
- toute modification des champs sensibles (superficie, géométrie, propriétaire, usage) nécessite validation par un profil autorisé ;
- aucune suppression définitive n'est autorisée : les enregistrements sont désactivés mais tracés
- les adresses doivent respecter une nomenclature standardisée ;
- aucune parcelle ne peut être enregistrée sans :
  - coordonnées GPS, ou
  - polygone géométrique
- aucun contribuable ne peut être actif sans NIF valide, sauf régime transitoire explicitement paramétré.

Ces règles structurent le fonctionnement quotidien du SIGREC et évitent :

- doubles enregistrements ;
- fausses adresses ;
- objets non géolocalisés ;
- pertes d'historique ;
- manipulations non tracées.

Elles garantissent que le référentiel reste unique, fiable, traçable et opposable dans le cadre de la gestion de l'assiette fiscale.

5.4.2 Module de gestion de l'assiette (IF - IRL - TAS)

Ce module regroupe l'ensemble des règles fonctionnelles permettant de déterminer l'assiette de l'impôt foncier, de l'impôt sur les revenus locatifs et de la taxe d'assainissement. Il exploite les données issues des référentiels pour qualifier les biens, calculer les surfaces imposables, identifier les loyers déclarés ou potentiels et appliquer les grilles tarifaires en vigueur. Il intègre la typologie des propriétés (résidentielle, commerciale, mixte), la situation d'occupation, le rang de localisation et la catégorie d'activité. Ce module est au cœur du système, car il transforme l'information physique et juridique en base taxable exploitable pour la liquidation.

Fonctions principales du module

Les principales fonctions assurées par ce module sont les suivantes :

- détermination automatique de l'assiette de l'IF à partir :
  - des superficies cadastrales et bâties
  - de la nature du bien (bâti / non bâti)
  - du rang de localisation
- détermination de l'assiette IRL à partir :
  - des loyers déclarés
  - des unités locatives identifiées
  - de la situation d'occupation (propriétaire occupant, locataire, vacant)
- détermination de l'assiette TAS à partir :
  - de la catégorie d'activité ou de l'usage des biens
  - du principe pollueur–payeur
- gestion des natures d'usage :
  - résidentiel
  - commercial
  - industriel
  - mixte
  - autres constructions
- classification automatique des biens selon :
  - nombre d'unités
  - type de bâtiment
  - statut d'occupation

- calcul des surfaces imposables à partir :
  - de la géométrie cadastrale
  - des données déclaratives vérifiées
- prise en compte des situations particulières :
  - bâtiments en construction
  - parcelles vacantes
  - bâtiments démolis
- génération d'alertes lorsque :
  - les déclarations sont incohérentes avec l'observation terrain
  - il existe un écart entre surface cadastrale et surface déclarée
  - un bien déclaré vacant présente des indices d'occupation

Ce module alimente ensuite le module de calcul et liquidation, mais il peut également produire des simulations de base taxable.

Règles de gestion associées
Le module applique un ensemble de règles de gestion structurantes, parmi lesquelles :
- aucune assiette fiscale n'est calculée sans existence préalable dans le référentiel parcellaire ;
- l'assiette IF est rattachée à la parcelle, pas uniquement au contribuable ;
- l'assiette IRL est rattachée aux unités locatives identifiées ;
- l'assiette TAS est rattachée à l'activité et/ou à l'usage du bien ;
- un bien ne peut être classé "non bâti" s'il existe un bâtiment cartographié ou observé ;
- un logement déclaré "occupé par le propriétaire" ne peut générer d'IRL, sauf cas spécifiques prévus ;
- toute modification de la base imposable (surface, usage, rang) doit être justifiée et validée ;
- un changement d'usage (résidentiel → commercial) entraîne une requalification automatique de l'assiette ;
- l'assiette peut être estimée d'office lorsqu'il existe :
  - refus de déclarer
  - incohérences manifestes
  - absence de NIF mais preuve d'activité
- les grilles tarifaires et les taux applicables sont paramétrables et historisés dans le système ;
- les situations suivantes déclenchent des contrôles automatiques :
  - IRL nul alors que plusieurs unités locatives sont déclarées
  - TAS nulle pour activité à forte production de déchets
  - IF basé sur surface manifestement sous-estimée par rapport au cadastre

Ces règles garantissent une assiette :
- plus complète ;
- plus objective ;
- plus équitable ;
- moins dépendante de la seule déclaration du contribuable.

Elles contribuent directement à la réduction de la sous-déclaration et à l'élargissement de la base taxable.

5.4.3 Module de gestion des droits et exonérations
Ce module permet d'appliquer, de suivre et de contrôler les régimes dérogatoires prévus par la réglementation : exonérations temporaires, permanentes, partielles ou conditionnelles. Il enregistre les motifs, la durée, les pièces justificatives et l'autorité ayant accordé la décision. Il garantit la traçabilité des avantages fiscaux et réduit les risques d'utilisation abusive. Grâce à lui, toute exonération est justifiable, datée et réversible, plutôt qu'une simple modification manuelle du montant d'impôt.

Fonctions principales du module
Les principales fonctions assurées par ce module sont les suivantes :
- enregistrement des demandes d'exonération formulées par les contribuables :
- qualification du type d'exonération :
  - permanente

  - temporaire
  - partielle
  - conditionnelle
- gestion des différentes catégories prévues par la loi :
  - biens publics
  - lieux de culte
  - associations reconnues
  - programmes sociaux
  - logements sociaux neufs, etc.
- enregistrement et gestion des pièces justificatives associées ;
- validation hiérarchique selon les niveaux de compétence (service, direction, autorité politique) ;
- détermination automatique de la période d'application :
  - date de début
  - date de fin
- prise en compte des droits dérivés :
  - réductions
  - abattements
  - moratoires
- suspension ou retrait d'exonération en cas de non-respect des conditions ;
- historisation complète des avantages fiscaux accordés à un contribuable, un bien ou une activité ;
- génération d'états de suivi des exonérations pour contrôle interne ou audit.

Ce module est directement connecté au module assiette et au module calcul et liquidation, afin que l'avantage fiscal soit appliqué correctement et de manière transparente.

Règles de gestion associées

Plusieurs règles de gestion structurantes sont appliquées par ce module :

- aucune exonération n'est accordée sans base légale ou réglementaire clairement référencée ;
- toute exonération doit être associée à :
  - un contribuable
  - une parcelle
  - une unité ou une activité
- l'exonération ne peut être saisie qu'avec :
  - pièces justificatives numérisées
  - décision d'autorité compétente
- toute exonération est limitée dans le temps, sauf mention explicite de permanence ;
- les exonérations permanentes font l'objet d'un réexamen périodique ;
- la fin d'exonération entraîne automatiquement recalcul de l'assiette et retour au régime normal ;
- les agents ne peuvent pas modifier directement le montant d'un impôt :
  - la réduction doit obligatoirement passer par ce module
- toute exonération :
  - est tracée
  - horodatée
  - liée à l'agent qui l'a traitée
- une même parcelle ne peut cumuler plusieurs exonérations incompatibles ;
- les exonérations partielles appliquent des taux ou abattements paramétrables ;
- des alertes sont déclenchées lorsque :
  - des exonérations inhabituelles sont observées
  - des renouvellements successifs apparaissent
  - un contribuable cumule plusieurs avantages sur différents biens

Ces règles permettent :

- d'éviter les exonérations arbitraires ;
- de sécuriser la décision administrative ;
- d'assurer une transparence totale vis-à-vis des contrôleurs et auditeurs ;
- de mesurer l'impact financier des politiques d'allègement fiscal.

5.4.4 Module de gestion des mutations foncières

Ce module traite les événements qui modifient la situation juridique ou physique d'une parcelle ou d'un bâtiment : mise en valeur, modification, morcellement, vente, succession, donation, fusion, division, changement de statut ou d'usage. Il assure la mise à jour des propriétaires et des titulaires de droits réels, tout en conservant l'historique complet des anciens propriétaires. Il permet également de suivre les subdivisions parcellaires et les extensions de constructions. Ce module est indispensable pour maintenir la correspondance entre la réalité foncière et la base fiscale.

Fonctions principales du module

Les principales fonctions assurées par ce module sont les suivantes :

- enregistrement des mutations juridiques :
  - vente
  - donation
  - succession
  - partage
  - adjudication
- mise à jour des propriétaires et titulaires de droits réels
- gestion des mutations physiques :
  - extension ou surélévation
  - démolition totale ou partielle
  - changement de configuration des bâtiments
- gestion des opérations sur parcelles :
  - mise en valeur
  - modification
  - fusion parcellaire
  - division parcellaire
  - remembrement
- enregistrement des changements d'usage :
  - résidentiel → commercial
  - commercial → mixte
  - terre agricole → lotissement bâti
- rattachement aux sources officielles :
  - actes notariés
  - certificats d'enregistrement
  - décisions judiciaires
  - permis de construire et d'habiter
- recalcul automatique des éléments impactés :
  - assiette IF
  - assiette IRL
  - catégorie TAS
- historisation complète :
  - anciens propriétaires
  - anciens usages
  - anciennes superficies ou géométries
- génération d'alertes en cas d'incohérences entre :
  - cadastre et fiscalité
  - déclaration du contribuable et observation terrain

Ce module est étroitement lié aux modules référentiels, assiette et contrôle terrain.

Règles de gestion associées

Pour sécuriser la gestion des mutations, plusieurs règles de gestion structurantes s'appliquent :

- toute mutation doit être associée à une pièce justificative officielle (notaire, cadastre, tribunal, urbanisme)
- un changement de propriétaire n'efface jamais l'ancien : il est archivé avec ses dates de validité
- une parcelle issue d'une division reçoit de nouveaux identifiants, l'ancien étant conservé comme "parcelle mère"

- en cas de fusion, les parcelles d'origine sont clôturées mais non supprimées
- toute modification des caractéristiques physiques (surface, géométrie, nombre d'unités) entraîne :
  - requalification de l'assiette
  - recalcul potentiel des impositions
- un changement d'usage entraîne automatiquement :
  - changement de catégorie fiscale
  - adaptation des taxes applicables
- aucune mutation n'est validée sans :
  - contrôle formel
  - agent habilité
- toute mutation est :
  - datée
  - horodatée
  - liée à un agent identifié
- en cas de succession, l'indivision peut être enregistrée en attendant le partage définitif
- des alertes sont générées lorsque :
  - plusieurs mutations successives apparaissent sur une courte période
  - des mutations sont enregistrées sans impact sur l'assiette alors qu'elles devraient en avoir
  - les informations cadastrales et fiscales divergent fortement

Ces règles garantissent que le répertoire reflète fidèlement la réalité foncière à tout moment, et que tout changement d'assiette repose sur une base juridique et technique solide.

5.4.5 Module de workflow d'enrôlement et de validation

Ce module organise et sécurise le processus d'intégration des informations dans le système. Toute création ou modification d'enregistrement suit un circuit de validation : saisie, contrôle, validation, mise en service. Les rôles sont différenciés selon les profils : agent de terrain, agent de saisie, superviseur, validateur hiérarchique. Le module évite les saisies unilatérales et garantit qu'aucune modification sensible (NIF, propriété, superficie, géométrie) ne soit validée sans contrôle préalable. Il structure ainsi la gouvernance fonctionnelle des données.

Fonctions principales du module

Le module de workflow d'enrôlement et de validation assure notamment les fonctions suivantes :

- gestion du processus complet d'enrôlement depuis la saisie initiale jusqu'à la validation finale
- enregistrement des demandes d'enrôlement provenant :
  - des équipes de recensement mobile
  - des guichets de la DGRK
  - du portail contribuable (auto déclaration)
- contrôle automatique de complétude des dossiers :
  - pièces jointes
  - coordonnées GPS
  - champs obligatoires
- attribution automatique d'un statut à chaque dossier :
  - brouillon
  - soumis
  - en vérification
  - validé
  - rejeté
- gestion des rôles et responsabilités :
  - agent de saisie
  - contrôleur
  - valideur hiérarchique
- traçabilité de chaque étape du traitement
- gestion des retours et corrections demandés au contribuable ou à l'agent
- validation progressive selon le type d'objet :
  - parcelle
  - bâtiment

  - unité locative
  - contribuable
  - activité
- activation automatique de l'objet après validation
- génération d'alertes pour les dossiers en attente ou en retard de traitement

Ce module constitue la colonne vertébrale de la gouvernance des données du SIGREC.

Règles de gestion associées
Pour sécuriser le processus, le module applique des règles claires :
- aucune donnée n'entre directement dans le référentiel sans validation
- toute création commence avec un statut provisoire (non opposable)
- seuls les profils autorisés peuvent :
  - valider une parcelle
  - modifier un propriétaire
  - approuver une géométrie
- toute modification d'un champ sensible (propriétaire, NIF, surface, usage, adresse) déclenche obligatoirement une revue par un valideur
- le rejet d'une demande doit être motivé par écrit et archivé
- aucun enregistrement ne peut être supprimé définitivement :
  - il est désactivé mais conservé dans l'historique
- le workflow est différent selon le canal d'entrée :
  - auto déclaration → contrôle renforcé
  - recensement terrain → contrôle de cohérence géographique
  - guichet → contrôle documentaire
- chaque étape est horodatée et associée à un utilisateur identifié
- un dossier ne peut passer à l'étape suivante qu'après satisfaction des champs obligatoires
- les dossiers en anomalie (adresse non localisée, NIF absent, surface incohérente) sont automatiquement orientés vers contrôle terrain

Ces règles garantissent :
- la qualité des données
- la traçabilité des décisions
- la limitation des risques de fraude
- la cohérence entre terrain, cadastre et fiscalité

Le workflow d'enrôlement et de validation est donc un élément clé de la fiabilité globale du SIGREC : il transforme la collecte brute en information validée et exploitable.

5.4.6 Module de contrôle et inspection terrain
Ce module soutient la planification et le suivi des activités de vérification sur le terrain. Il permet de générer des listes de contrôle à partir d'alertes : bâtis non déclarés, loyers incohérents, absence de NIF, divergences entre cadastre et fiscalité, etc. Il gère les tournées des équipes, les constats, les photos géolocalisées et les rapports d'inspection. Les résultats des contrôles alimentent ensuite automatiquement les autres modules (assiette, contentieux, mise à jour des référentiels). Il est donc l'outil clé d'une fiscalité proactive fondée sur la vérification.

Fonctions principales du module
Le module de contrôle et d'inspection terrain comprend notamment les fonctions suivantes :
- planification des missions de contrôle :
  - ciblées sur zones ou quartiers
  - ciblées sur types d'activité
  - ciblées sur anomalies détectées par le système
- génération de listes de parcelles à vérifier à partir :
  - alertes du module assiette
  - croisements avec cadastre, SNEL, REGIDESO
  - signalements des contribuables

- affectation des contrôles aux équipes ou agents nommément désignés
- utilisation d'une application mobile pour :
  - collecte de photos géolocalisées
  - saisie de constats sur le terrain
  - mise à jour des statuts d'occupation
  - relevé des coordonnées GPS
- vérification de :
  - l'existence réelle des bâtiments
  - le nombre d'unités locatives
  - l'usage réel (résidentiel, commercial, mixte)
  - la présence d'activité économique
- constatation des infractions :
  - absence de déclaration
  - fausse déclaration
  - construction non autorisée
- transmission automatique des résultats vers :
  - module assiette pour requalification
  - module contentieux pour poursuites
  - module mutations pour mise à jour
- production de rapports d'inspection terrain individuels ou consolidés
- suivi des performances des équipes terrain (tournées réalisées, dossiers traités)

Ce module permet de passer d'une fiscalité déclarative à une fiscalité vérifiée sur le terrain.

Règles de gestion associées
Pour garantir la qualité et la valeur probante des contrôles, le module applique plusieurs règles de gestion:

- aucun contrôle terrain n'est anonyme :
  - chaque mission est assignée à un agent identifié
- toute constatation doit être :
  - datée
  - géolocalisée
  - associée à un enregistrement dans SIGREC
- une photo non géolocalisée ne peut servir de justificatif principal
- un changement de statut d'occupation ou d'usage requiert une preuve terrain :
  - photo
  - procès-verbal
  - témoignage administratif
- les contrôles peuvent être :
  - aléatoires
  - déclenchés par alertes système
  - déclenchés par plainte ou signalement
- les constats terrain priment sur :
  - les déclarations non justifiées du contribuable
- toute anomalie critique identifiée sur le terrain entraîne :
  - requalification automatique de l'assiette
  - saisine du contentieux si nécessaire
- il est interdit à l'agent terrain de liquider directement un impôt :
  - son rôle est la constatation, pas la taxation
- les missions de contrôle font l'objet :
  - d'un rapport
  - d'une validation hiérarchique
  - d'un archivage

Ces règles assurent :

- la fiabilité juridique des constats
- la protection des agents et des contribuables
- la traçabilité des interventions
- la crédibilité des procédures de contrôle.

5.4.7 Module de gestion des déclarations et auto-déclarations

Ce module permet aux redevables ou à leurs représentants de déposer en ligne ou au guichet leurs déclarations d'IF, d'IRL ou de TAS. Il gère également les mises à jour volontaires : changement de locataire, modification d'activité, ajustement de l'usage des locaux. Il applique des contrôles de cohérence avant acceptation et peut déclencher automatiquement des demandes de pièces justificatives ou des contrôles terrain. Ce module contribue à simplifier la relation entre administration et contribuable tout en améliorant la qualité des données recueillies.

Fonctions principales du module

Les principales fonctions couvertes par ce module sont :

- dépôt de déclarations initiales :
  - création d'un nouveau bien imposable
  - début d'activité locative
  - création d'activité génératrice de TAS
- dépôt de déclarations modificatives portant sur :
  - changement d'usage
  - changement d'occupation
  - modification des loyers déclarés
  - ajout ou suppression d'unités locatives
- gestion des auto-déclarations en ligne via portail contribuable ;
- saisie assistée au guichet pour les contribuables non connectés ;
- prise en charge des déclarations issues :
  - du recensement terrain
  - des opérations de contrôle
- dépôt des pièces justificatives numérisées ;
- contrôle automatique de complétude des données avant soumission ;
- attribution d'un numéro unique de déclaration ;
- suivi de l'état de traitement :
  - soumis
  - en cours d'examen
  - accepté
  - rejeté
- génération de récépissés électroniques de déclaration ;
- historisation de toutes les déclarations d'un contribuable ou d'un bien ;
- alimentation automatique des modules assiette, liquidation et contrôle.

Ce module permet d'encadrer la relation déclarative tout en facilitant l'accès du contribuable au service public fiscal.

Règles de gestion associées

Le module applique plusieurs règles essentielles pour sécuriser et fiabiliser les déclarations :

- toute déclaration doit être rattachée à un NIF valide, sauf cas transitoires autorisés ;
- une déclaration ne devient opposable qu'après :
  - examen
  - validation
  - enregistrement définitif
- aucune déclaration ne peut être validée sans :
  - adresse normalisée
  - localisation GPS ou parcellaire
- les informations impactant l'assiette (surface, usage, loyers) sont soumises à :
  - contrôle documentaire
  - ou contrôle terrain en cas de doute
- toute modification d'une déclaration validée crée une nouvelle version :
  - l'ancienne est archivée
  - jamais supprimée
- le défaut de déclaration dans les délais peut déclencher :
  - taxation d'office

    - pénalités prévues par les textes
- l'auto-déclaration n'est pas automatiquement acceptée :
    - elle suit le workflow d'enrôlement et validation
- une unité locative déclarée "vacante" sur longue durée fait l'objet d'alerte automatique ;
- en cas de contradiction entre :
    - déclaration
    - constat terrain
    - données partenaires (SNEL, REGIDESO, cadastre)
      le système déclenche un contrôle ciblé
- toute déclaration rejetée est motivée et consultable par le contribuable.

Ces règles permettent :
- d'encourager la déclaration volontaire ;
- de limiter la fraude déclarative ;
- de formaliser la relation usager–administration ;
- de fiabiliser l'assiette avant liquidation.

5.4.8 Module de calcul et de liquidation

Ce module traduit les règles fiscales en montants à payer. Il applique les barèmes, taux et assiettes définis par la réglementation à partir des données validées par les modules précédents. Il permet la simulation, le recalcul après contrôle, la génération automatique des montants d'IF, d'IRL et de TAS et la prise en compte des exonérations et pénalités. Il assure l'homogénéité des pratiques de liquidation et supprime les calculs manuels sources d'erreurs et de contestation.

Fonctions principales du module

Les principales fonctions assurées par ce module sont les suivantes :
- calcul automatique de l'impôt foncier (IF) à partir :
    - de la base imposable déterminée par l'assiette
    - de la nature bâtie ou non bâtie
    - du rang de localisation et de la catégorie du bien
- calcul automatique de l'IRL à partir :
    - des loyers déclarés ou estimés d'office
    - de la nature des contrats locatifs
    - du nombre et du type d'unités locatives
- calcul automatique de la TAS à partir :
    - de la catégorie d'activité
    - de l'usage effectif des locaux
    - de la production potentielle de déchets
- prise en compte automatique :
    - des exonérations
    - des abattements
    - des réductions légales
- application des pénalités et majorations en cas :
    - de retard de paiement
    - de non-déclaration
    - de déclaration inexacte
- simulation des montants avant validation définitive ;
- recalcul après mutation, changement d'usage ou correction d'assiette ;
- génération du détail de calcul consultable pour audit ou contestation ;
- historisation des calculs successifs pour un même bien ou contribuable ;
- paramétrage centralisé des :
    - barèmes
    - taux
    - coefficients
    - pénalités
- production automatique des montants liquides transmis au module d'émission des titres ;

Ce module est connecté au module assiette, au module droits et exonérations et au module émission des titres.

Règles de gestion associées
Afin d'assurer l'équité et la conformité légale des liquidations, le module applique des règles de gestion strictes :

- aucun calcul n'est réalisé sans assiette validée ;
- toute modification de base imposable entraîne automatiquement le recalcul ;
- les paramètres de calcul sont :
  - centralisés
  - contrôlés
  - historisés
- les agents ne peuvent pas modifier directement un montant d'impôt :
  - ils modifient la donnée source
  - le système recalcule automatiquement
- les pénalités sont appliquées selon :
  - des taux paramétrables
  - des règles de délais prévues par les textes
- le système empêche :
  - les doubles liquidations pour une même période
- toute liquidation génère :
  - un numéro unique
  - une trace horodatée
  - l'identification de l'agent ou du processus à l'origine du calcul
- le contribuable peut consulter :
  - la base
  - le barème
  - le détail du calcul utilisé
- les calculs d'office ne peuvent être validés qu'après :
  - contrôle préalable
  - ou constat d'absence de déclaration
- toute correction rétroactive est :
  - justifiée
  - approuvée
  - tracée

Ces règles garantissent un système :

- transparent
- vérifiable
- auditable
- conforme aux textes.

5.4.9 Module d'émission des titres et notifications

Ce module génère les documents officiels adressés aux redevables : avis d'imposition, titres de perception, rappels et mises en demeure. Il constitue le point de passage entre la liquidation de l'impôt et la phase de recouvrement. Il permet l'édition et la diffusion multicanal des documents (impression papier, SMS, e-mail, portail contribuable) et assure le suivi complet de leur notification. Ce module est essentiel pour formaliser la créance fiscale, sécuriser la preuve de notification et enclencher, le cas échéant, les procédures de recouvrement amiable ou forcé. Il garantit également l'uniformité des modèles et la traçabilité des documents émis.

Fonctions principales du module
Les principales fonctions de ce module sont les suivantes :

- génération automatique :
  - d'avis d'imposition
  - de titres de perception
  - de rappels de paiement

    - de mises en demeure
- production en masse ou au cas par cas ;
- personnalisation des documents selon :
    - type d'impôt (IF, IRL, TAS)
    - période d'imposition
    - statut du contribuable
- insertion automatique dans les documents :
    - identifiants du contribuable et du bien
    - base d'imposition
    - détail du calcul
    - montant dû et échéances
- numérotation unique des titres émis ;
- gestion des canaux de notification :
    - impression et distribution physique
    - téléchargement via portail contribuable
    - envoi par e-mail
    - SMS de rappel
- suivi du statut de notification :
    - généré
    - envoyé
    - remis
    - non remis
    - contesté
- historisation de tous les documents émis pour un contribuable ou un bien ;
- génération de listes pour distribution terrain ou par postes communaux ;
- alimentation automatique des modules :
    - recouvrement
    - contentieux
- possibilité d'annulation ou de réémission contrôlée d'un titre.

Ce module établit donc la preuve d'information du contribuable et matérialise la créance de la DGRK.

Règles de gestion associées
Pour encadrer l'émission et la notification des titres, le module applique des règles de gestion strictes :

- aucun titre ne peut être émis sans liquidation valide ;
- chaque titre porte :
    - un identifiant unique
    - la référence juridique
    - la période concernée
- la modification manuelle du montant d'un titre est interdite :
    - toute modification passe par recalcul
- la notification est réputée faite lorsque :
    - remise avec signature
    - ou mise à disposition sur portail, notifiée par SMS / e-mail
- toute annulation de titre doit être :
    - motivée
    - approuvée par un profil habilité
    - archivée
- les titres non remis déclenchent automatiquement :
    - nouvelle tentative
    - ou procédure alternative de notification
- la mise en demeure ne peut être émise qu'après :
    - non-paiement après échéance
    - ou absence de réaction aux premiers rappels
- l'émission en masse est limitée aux profils autorisés
- en cas de contestation, le titre est marqué :
    - "sous recours"

  - sans être effacé du système
- les supports de notification sont conservés :
  - bordereau de distribution
  - accusé de réception
  - preuve électronique d'envoi

Ces règles permettent :
- la sécurité juridique de la notification
- la traçabilité complète des échanges
- l'harmonisation des pratiques
- la préparation des procédures de recouvrement et contentieux.

5.4.10 Module de contentieux et sanctions

Ce module gère les situations de non-conformité à la législation fiscale locale : défaut ou retard de déclaration, sous-déclaration, absence de paiement, opposition au contrôle, fausse information ou fraude avérée. Il permet d'enregistrer les infractions constatées, de qualifier juridiquement les manquements et de déclencher les pénalités administratives ou financières correspondantes. Il suit l'ensemble des étapes du contentieux, depuis la contestation du contribuable jusqu'à la décision définitive, le recours éventuel et l'apurement de la dette. Ce module garantit la cohérence entre la base fiscale, les mesures coercitives appliquées et l'historique du redevable, contribuant ainsi à la crédibilité de l'impôt et au respect volontaire des obligations fiscales.

Fonctions principales du module

Les principales fonctions de ce module sont les suivantes :
- enregistrement des infractions constatées :
  - défaut de déclaration
  - déclaration inexacte ou mensongère
  - absence ou retard de paiement
  - non-présentation aux contrôles
  - usage frauduleux d'exonérations
- qualification juridique des manquements selon les textes applicables
- calcul et application automatiques :
  - amendes
  - pénalités
  - majorations
  - intérêts de retard
- gestion des procédures de contentieux :
  - contestation gracieuse ou hiérarchique
  - instruction du dossier
  - prise de décision
  - voies de recours
- suivi du statut du dossier :
  - ouvert
  - en instruction
  - en décision
  - en recours
  - apuré
- gestion des plans d'apurement ou échéanciers de paiement
- liaison automatique avec :
  - module de contrôle terrain
  - module d'émission des titres
  - module de recouvrement
- production des documents officiels de procédure :
  - procès-verbaux
  - notifications de pénalités
  - décisions de contentieux
- historisation intégrale du litige pour audit ou contrôle interne

- suivi des résultats : sanctions appliquées, montants récupérés, abandons

Ce module permet à l'administration de traiter les non-conformités de façon structurée, équitable et traçable.

Règles de gestion associées
Pour encadrer les procédures coercitives, plusieurs règles de gestion s'appliquent :
- aucune sanction ne peut être appliquée sans :
  - constat d'infraction
  - base légale clairement identifiée
- toute pénalité est liée à :
  - un contribuable
  - un bien ou une activité
  - une période déterminée
- le montant de la pénalité est calculé automatiquement à partir :
  - des taux en vigueur
  - de la durée du manquement
  - du type d'infraction
- toute contestation suspend certains effets, selon la législation en vigueur
- les décisions doivent être :
  - motivées par écrit
  - notifiées au contribuable
- aucune infraction ni sanction n'est supprimée du système :
  - elles sont apurées ou clôturées
- les sanctions sont graduées selon la gravité :
  - rappel et pénalités
  - mise en demeure
  - poursuites contentieuses
- les agents ne peuvent pas annuler une sanction sans :
  - habilitation spécifique
  - justification enregistrée dans le système
- les dossiers de fraude présumée font l'objet :
  - d'une instruction particulière
  - d'une transmission aux autorités compétentes si nécessaire
- le module déclenche automatiquement des sanctions dans les cas suivants :
  - absence de déclaration après relance
  - non-paiement après échéance
  - constat de fausse déclaration vérifiée terrain

Ces règles visent à assurer :
- équité de traitement entre contribuables
- sécurité juridique des décisions
- transparence et traçabilité des procédures
- dissuasion des comportements frauduleux

Le module de reporting et de tableaux de bord fournit aux gestionnaires, aux responsables opérationnels et aux décideurs des outils d'analyse et de suivi de la performance fiscale. Il consolide les données issues des différents modules du SIGREC pour produire des indicateurs fiables portant sur l'évolution de l'assiette, les liquidations, les recouvrements, la couverture du territoire, les contrôles réalisés et l'activité des équipes. Il permet la production d'états standardisés, exigés par la réglementation ou par la hiérarchie, ainsi que de rapports analytiques plus avancés. Ce module constitue un levier central pour renforcer la transparence, objectiver les décisions et piloter stratégiquement les recettes locales.

Fonctions principales du module
Les principales fonctions assurées par ce module sont les suivantes :
- production d'états statistiques standard sur :
  - nombre de parcelles et unités enregistrées

    - évolution de l'assiette IF, IRL, TAS
    - montants liquidés par période et par zone
    - montants recouvrés et taux de recouvrement
- génération de tableaux de bord dynamiques pour :
    - directions centrales
    - services communaux
    - équipes de terrain
- ventilation des indicateurs par :
    - commune, quartier, avenue
    - type d'impôt ou de taxe
    - catégorie d'activité
    - type de contribuable
- suivi des performances opérationnelles :
    - activités de recensement
    - dossiers traités
    - contrôles réalisés
    - anomalies corrigées
- comparaison entre :
    - potentiel fiscal estimé
    - assiette constituée
    - montants effectivement recouvrés
- génération d'états destinés :
    - aux autorités locales
    - aux partenaires techniques et financiers
    - aux organes de contrôle
- possibilité de requêtes ad hoc pour analyses spécifiques
- exportation des rapports en formats usuels :
    - PDF
    - Excel
    - CSV
- alimentation automatique de la cartographie SIG pour analyses spatiales
- mise en place d'alertes et de seuils (sous-performance, chute de rendement, anomalies)

Ce module transforme le SIGREC d'outil d'enregistrement en véritable outil d'aide au pilotage.

Règles de gestion associées
Pour garantir la fiabilité et la lisibilité des informations produites, plusieurs règles de gestion s'appliquent :

- les indicateurs reposent sur des référentiels uniques :
    - même définition
    - même périmètre
    - même période
- les tableaux de bord sont automatiquement mis à jour à partir des modules sources
- les agents ne peuvent pas modifier les résultats des indicateurs :
    - seules les données sources peuvent être corrigées
- toute modification d'un indicateur structurel doit être :
    - documentée
    - approuvée
    - historisée
- distinction obligatoire entre :
    - liquidé
    - recouvré
    - restant dû
- les résultats sont ventilés par période :
    - mensuelle
    - trimestrielle
    - annuelle
- les comparaisons interannuelles sont basées sur :

  - mêmes périmètres géographiques
  - mêmes définitions d'impôts et taxes
- les données sensibles sont accessibles selon des profils et habilitations définis
- certains états "officiels" sont figés après validation afin de servir de référence

Ces règles garantissent que les rapports produits sont :
- fiables
- comparables dans le temps
- auditables
- opposables comme documents officiels.

5.4.11 Module de cartographie SIG et analyses spatiales

Le module de cartographie SIG et d'analyses spatiales constitue le marqueur distinctif du SIGREC. Il permet de représenter sur des cartes interactives l'ensemble des objets fiscaux : parcelles, bâtiments, unités locatives, activités économiques et impositions y afférentes. Il offre la capacité de produire des cartes thématiques pour analyser la densité fiscale, identifier les zones non couvertes, détecter le bâti non déclaré et étudier la corrélation avec d'autres réseaux et services urbains (eau, électricité, voirie, assainissement). Ce module transforme les données fiscales en information géographique exploitable, faisant du SIGREC non seulement un outil de gestion fiscale, mais aussi un instrument d'analyse territoriale et d'aide à la planification urbaine.

Fonctions principales du module

Les principales fonctions assurées par ce module sont les suivantes :
- visualisation cartographique :
  - des parcelles cadastrales
  - des bâtiments et constructions
  - des unités locatives et activités économiques
  - des contribuables géolocalisés
- superposition de différentes couches d'information :
  - couches cadastrales
  - imagerie satellitaire
  - couches fiscales (IF, IRL, TAS)
  - réseaux techniques (électricité, eau, voirie, assainissement)
- production de cartes thématiques, par exemple :
  - densité de parcelles imposables
  - répartition des recettes par quartier
  - zones non recouvertes par le recensement
  - bâti non déclaré ou sous-déclaré
  - zones à forte vacance locative
- requêtes spatiales interactives :
  - sélectionner toutes les parcelles dans un périmètre donné
  - identifier les bâtiments situés dans une zone ciblée
  - croiser imposition et localisation
- localisation et suivi des opérations terrain :
  - missions de contrôle
  - tournées de recensement
- impression de cartes thématiques pour :
  - rapports officiels
  - réunions de décision
  - communication aux autorités locales
- mesure et calcul géométrique :
  - superficies
  - distances
  - périmètres
- détection automatisée d'anomalies spatiales :
  - parcelles sans imposition
  - bâtiments visibles sur image sans enregistrement fiscal

  - divergences entre cadastre et référentiel fiscal
- export de données cartographiques vers d'autres systèmes SIG

Ce module place la dimension spatiale au cœur de la gestion fiscale locale et de l'identification du potentiel fiscal.

Règles de gestion associées
Pour garantir la fiabilité et l'usage correct des analyses spatiales, plusieurs règles de gestion s'appliquent:
- toute parcelle doit être géolocalisée par coordonnées ou polygone pour être visible sur la carte
- aucune mise à jour géométrique (surface, limites) ne peut être validée sans contrôle habilité
- les couches officielles (cadastre, limites administratives, voirie) sont :
  - identifiées comme référentiels
  - historisées lorsqu'elles sont mises à jour
- les images satellitaires ou ortho-photos utilisées doivent être :
  - datées
  - référencées
  - associées à leur source
- les cartes produites à des fins officielles portent :
  - légende
  - échelle
  - date de génération
- les informations nominatives affichées sur carte respectent :
  - les règles de confidentialité
  - les habilitations d'accès
- toute anomalie spatiale détectée (bâti non déclaré, parcelle non imposée) génère :
  - une alerte
  - éventuellement une mission de contrôle terrain
- la suppression d'une géométrie existante est interdite :
  - seule la désactivation avec historique est autorisée
- la cohérence entre :
  - assiette
  - géométrie
  - référentiel parcellaire est systématiquement vérifiée par le système

5.4.12 Module d'aide à la décision
Le module d'aide à la décision synthétise l'ensemble des données produites par le SIGREC pour orienter les priorités d'action de la DGRK. Il permet d'identifier le potentiel fiscal inexploité, de détecter les zones à forte probabilité de fraude ou de sous-déclaration, et d'évaluer l'impact de différentes options de gestion ou de réforme. Il offre des outils de simulation, de projection et de scénarisation qui soutiennent la planification budgétaire et stratégique. Ce module place la DGRK dans une logique de gouvernance par la donnée, où les choix ne reposent plus uniquement sur l'intuition ou l'expérience, mais sur une analyse consolidée, objectivée et mesurable.

Fonctions principales du module
Les principales fonctions assurées par ce module sont les suivantes :
- estimation du potentiel fiscal théorique à partir :
  - du nombre de parcelles et unités
  - des loyers moyens par zone
  - des catégories d'activité
- identification du potentiel fiscal inexploité en comparant :
  - assiette théorique
  - assiette constituée
  - recettes effectivement recouvrées
- détection de zones à risque élevé de fraude ou sous-déclaration :
  - discordance entre consommation d'eau/électricité et loyers déclarés
  - bâtiments visibles non enregistrés
  - IRL nul dans zones fortement locatives

- simulation de scénarios, par exemple :
  - augmentation des taux
  - élargissement de l'assiette
  - changement de politique d'exonération
- évaluation de l'impact de :
  - campagnes de recensement
  - contrôles ciblés
  - régularisations massives
- priorisation géographique des actions :
  - quartiers prioritaires
  - activités à fort rendement
- suivi de la contribution de chaque :
  - commune
  - quartier
  - type d'impôt ou activité
- outils d'analyse prédictive :
  - projection des recettes
  - estimation des risques d'impayés
- génération d'indicateurs pour la programmation budgétaire locale ;
- mise à disposition d'outils d'aide à la décision pour :
  - direction générale
  - tutelle
  - élus locaux

Ce module transforme le SIGREC en véritable instrument de pilotage stratégique des finances locales.

Règles de gestion associées

Plusieurs règles encadrent le fonctionnement du module d'aide à la décision :

- les simulations n'ont pas d'effet direct sur les données réelles :
  - elles se font dans un environnement de projection
- les hypothèses utilisées dans chaque scénario sont :
  - explicitées
  - enregistrées
  - historisées
- toute projection financière est datée et liée à une période de référence
- la distinction est systématiquement faite entre :
  - potentiel théorique
  - assiette constatée
  - recettes encaissées
- les modèles utilisés pour estimation sont validés par l'administration
- les résultats exposés tiennent compte :
  - des exonérations légales
  - des contraintes sociales et économiques
- certaines analyses sensibles sont accessibles uniquement à des profils habilités
- les décisions prises à partir de ces analyses sont traçables, ce qui facilite l'audit et l'évaluation des politiques publiques

Ces règles garantissent un usage rigoureux et responsable de l'analytique décisionnelle, tout en exploitant la pleine valeur des données collectées par le SIGREC.

Avec ce module, la DGRK passe d'une logique de simple enregistrement à une logique :

- ***d'anticipation ;***
- ***de priorisation ;***
- ***d'optimisation continue des recettes.***

5.4.13 Conclusion de la conception fonctionnelle

Le répertoire cible SIGREC permet :

- d'ancrer la fiscalité sur des objets réels ;

- de suivre les biens et activités dans le temps ;
- d'intégrer la dimension géographique ;
- d'unifier IF, IRL et TAS ;
- de sécuriser et d'élargir l'assiette fiscale.

On passe ainsi d'une administration qui attend la déclaration à une administration qui observe, vérifie, géolocalise et recoupe

5.5 Schéma des données

5.5.1 Nouveau contenu des fichiers d'identification parcellaires

Le fichier d'identification doit être **parcellaire** et non uniquement **contribuable**. L'approche doit être axée sur l'objet physique de l'impôt que sur l'individu seul. L'unité de base de la taxation (la parcelle) doit être identifiée par un point géographique (coordonnées GPS) et/ou un polygone (surface). Cette identification spatiale est la clé de voûte de la sécurisation de l'assiette.

5.5.2 Champs essentiels (NIF, Statuts, foncier, type de propriété)

Il est primordial d'enrichir la fiche d'identification par des données permettant la déclaration précise et la vérification des déclarations. Ces champs sont conçus pour établir une cartographie complète et fiable de l'assiette.

Tableau 3 : Nouveau contenu des fichiers d'identification parcellaires

Catégorie de champ	Nom du champ	Type de donnée	Statut	Rôle fiscal
Identification fiscale	NIF contribuable	Alphanumérique	Obligatoire (clé primaire)	Identification unique, lutte contre les doublons. L'usage du NIF est un prérequis légal à consolider
Identification foncière	ID cadastral unique	Alphanumérique	Obligatoire (clé étrangère)	Lien avec la source légale de propriété. Ce champ garantit la légitimité du propriétaire taxé.
Identification spatiale	Coordonnées GPS (X, Y)	Géospatial (point/polygone)	Obligatoire	Géolocalisation, VFE, cartographie. Ces données permettent une analyse spatiale et une gestion visuelle de l'assiette
Description du bien	Surface totale / Surface bâtie	Numérique (m^2)	Obligatoire	Base de calcul de l'IF. La précision de ces données est essentielle à l'équité.
Usage du bien	Type de propriété (résidentiel, commercial, mixte, autre construction, etc.)	Liste déroulante	Obligatoire	Détermination de l'assiette IRL et TA. Ce champ permet la qualification juste des revenus locatifs potentiels.

5.5.3 Structuration des données : parcelle, contribuable et relations associées

La mise en place du registre repose sur une organisation claire des informations. L'entité principale est la parcelle, à laquelle sont rattachées les données relatives aux contribuables. Les tableaux ci-après présentent, d'abord, les champs essentiels de la parcelle, ensuite ceux du contribuable, puis le schéma de liaison entre les deux entités afin d'assurer la traçabilité des droits, des mutations et de la fiscalité associée.

Tableau 4 : Champs de la parcelle (entité principale)

Catégorie	Champ essentiel	Type	Statut	Rôle
Identification parcelle	Identifiant cadastral unique	Alphanumérique	Obligatoire	Identifiant principal du registre
Localisation	Adresse / description	Texte	Obligatoire	Repérage administratif
Spatial	Coordonnées GPS / polygone	Géospatial	Obligatoire	Cartographie et contrôle terrain
Surface	Surface cadastrale	Numérique	Obligatoire	Base de calcul fiscal
Surface	Surface bâtie	Numérique	Obligatoire	Détermination IF
Typologie	Type de propriété	Liste	Obligatoire	Résidentiel, commercial, mixte, etc.
Occupation	Statut d'occupation	Liste	Obligatoire	Occupé, vacant, en construction
Usage	Affectation principale	Liste	Obligatoire	IRL, TAS, activité économique
Titres	Référence du certificat / bail	Texte	Obligatoire	Sécurisation juridique
Mutations	Historique des transferts	Journal	Obligatoire	Traçabilité
Statut fiscal	Actif, suspendu, litigieux, radié	Liste	Obligatoire	Gestion du contentieux

Tableau 5 : Champs du contribuable / propriétaire

Catégorie	Champ essentiel	Type	Statut	Rôle
Identification	Nom / raison sociale	Texte	Obligatoire	Identification du redevable
Identification	NIF	Alphanumérique	Conditionnel	Interopérabilité fiscale et dédoublonnage
Identification civile	CIN / RCCM	Alphanumérique	Conditionnel	Preuve d'identité
Contact	Adresse	Texte	Recommandé	Notification
Contact	Téléphone	Numérique	Recommandé	Relances
Contact	Email	Texte	Recommandé	Dématérialisation
Statut	Personne physique / morale	Liste	Obligatoire	Régime applicable
Situation	Résident / non-résident	Liste	Recommandé	Fiscalité différenciée
Historique	Antécédents fiscaux	Journal	Recommandé	Suivi des arriérés

Tableau 6 : Lien entre parcelle et contribuable
(Relation propriétaire-parcelle, plusieurs cas possibles)

Champ	Type	Statut	Description
Identifiant de la parcelle	Référence	Obligatoire	Clé étrangère vers la parcelle
Identifiant du contribuable (NIF)	Référence	Obligatoire	Clé étrangère vers le contribuable
Type de lien	Liste	Obligatoire	Propriétaire, usufruitier, locataire principal, gestionnaire
Quote-part	Numérique (%)	Conditionnel	Cas de copropriété
Date de début de droit	Date	Obligatoire	Entrée dans le patrimoine
Date de fin de droit	Date	Conditionnel	Mutation, succession, cession
Statut du lien	Liste	Obligatoire	Actif, résilié, litigieux
Base juridique	Texte	Recommandé	Titre foncier, jugement, bail
Historique	Journal	Obligatoire	Traçabilité complète des changements

5.5.4 Processus d'actualisation et de sécurisation des données

Un système d'information n'est réellement fiable que s'il reste à jour et sécurisé dans la durée. La qualité des décisions fiscales et la crédibilité du registre dépendent donc autant de la conception initiale que de la capacité à corriger, compléter et tracer les informations tout au long du cycle de vie du système. Le dispositif proposé combine actualisation continue sur le terrain, échanges automatiques avec les institutions partenaires et règles strictes de sécurisation fonctionnelle.

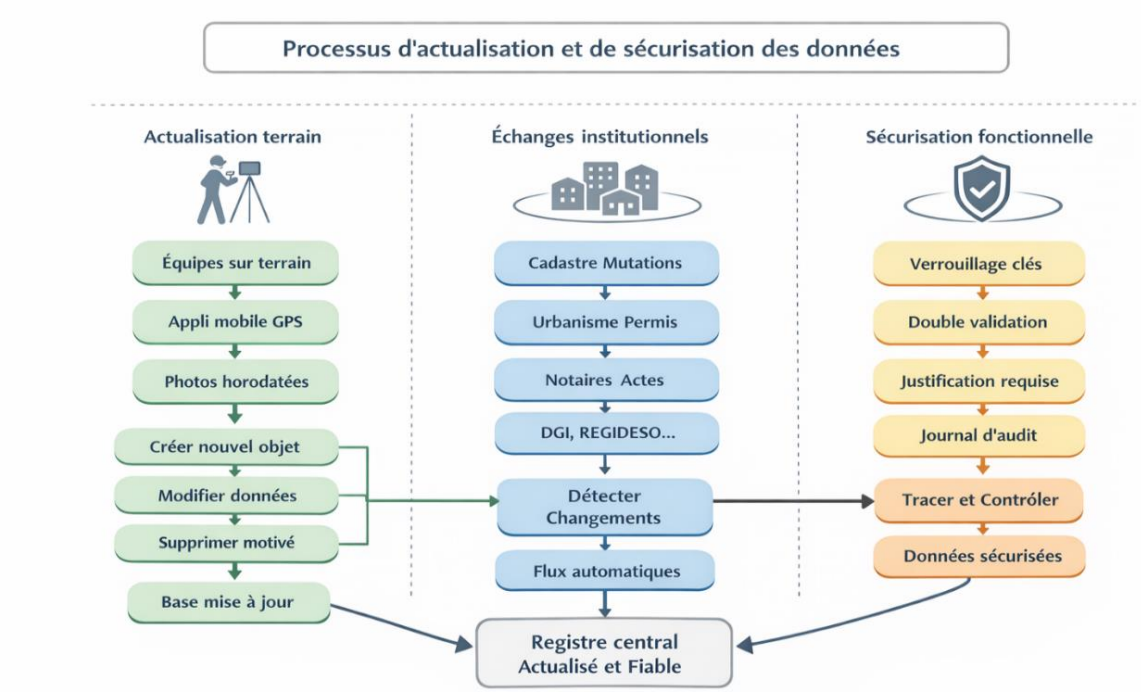

Figure 4 : Processus d'actualisation et de sécurisation des données

5.5.5 Actualisation continue (recensement roulant)

Le SIGREC repose sur un principe d'actualisation permanente. Il ne s'agit pas d'un recensement ponctuel, mais d'un processus dynamique et régulier. Pour cela, le système intègre :

- des équipes de vérification sur le terrain
- une application mobile utilisable en ligne et hors ligne
- la capture de photos géolocalisées
- un horodatage automatique de chaque opération

Chaque mission de terrain peut entraîner différentes actions :

- création d'un nouvel objet tel qu'une parcelle bâtie, un bâtiment secondaire, une unité locative ou une activité économique
- modification d'une donnée existante comme la surface, l'usage, le statut d'occupation ou le nombre d'unités louées
- suppression ou annulation d'un enregistrement, avec justification obligatoire et traçabilité complète

Ce mécanisme de recensement roulant permet d'éviter les bases figées. Il soutient une fiscalité plus équitable, fondée sur des données actuelles et vérifiables.

5.5.6 Flux d'échanges institutionnels

L'actualisation ne repose pas uniquement sur le travail de terrain. Le système reçoit aussi des informations en provenance d'autres institutions publiques. Ces échanges structurés et automatiques limitent les omissions et améliorent l'interopérabilité.

Le système cible est alimenté par les flux suivants :

- cadastre pour les mutations foncières

- services d'urbanisme pour les autorisations de bâtir et les permis
- notaires pour les actes de vente et les baux notariés
- REGIDESO ou SNEL pour les nouveaux raccordements aux réseaux
- direction des impôts pour l'attribution des NIF
- communes pour les autorisations d'ouverture d'activités

Ces échanges permettent de détecter rapidement :

- les nouvelles constructions et extensions
- les subdivisions de parcelles
- les changements de propriétaires
- les locations déclarées auprès d'autres services mais absentes dans la base fiscale

Le croisement des sources renforce la complétude du registre et réduit la fraude et l'évasion fiscale.

5.5.7 Sécurisation et audit

La sécurité ne se limite pas aux aspects techniques. Elle repose aussi sur des règles fonctionnelles claires, compréhensibles par les utilisateurs et intégrées directement dans le système.

Les principales mesures prévues sont les suivantes :

- impossibilité de supprimer définitivement un enregistrement
- verrouillage des champs clés après validation
- justification obligatoire pour toute modification sensible
- double validation en cas de changement de propriétaire ou de transfert de droits

Un journal d'audit complet enregistre systématiquement :

- l'utilisateur concerné
- la nature de la modification
- la date et l'heure de l'action
- l'objet concerné dans le registre

Ce dispositif garantit la traçabilité des opérations et protège l'administration contre les manipulations abusives. Il renforce aussi la confiance des usagers dans l'équité et la transparence du système.

6. Architecture technique du répertoire cible (SIGREC/DGRK)

La présente section décrit la conception technique et l'architecture cible du système SIGREC. Elle traduit les choix fonctionnels présentés précédemment en un dispositif technique cohérent, sécurisé et évolutif. L'objectif n'est pas encore de procéder au dimensionnement détaillé des équipements, mais de définir l'organisation globale du système, ses principaux composants techniques, les modes d'interconnexion des sites et les principes structurants qui guideront les étapes ultérieures du projet.

L'architecture proposée vise à garantir la fiabilité du répertoire automatisé des contribuables, l'intégration des fonctionnalités fiscales et géospatiales, l'interopérabilité avec les administrations partenaires ainsi que la capacité à connecter l'ensemble des services déconcentrés impliqués dans la gestion de l'impôt foncier, de l'IRL et de la taxe d'assainissement. Elle prend également en compte les contraintes locales, notamment la disponibilité de l'énergie électrique et la nécessité de renforcer l'alimentation des sites par des solutions photovoltaïques.

Cette section présente successivement les principes directeurs de conception technique, l'architecture technique et applicative globale, l'architecture des données et des échanges, puis l'infrastructure matérielle et l'interconnexion des différents sites de la DGRK.

6.1 Principes directeurs de la conception technique

La conception technique du SIGREC repose sur un ensemble de principes directeurs destinés à garantir la fiabilité, la pérennité et l'évolutivité du système. Ces principes orientent les choix d'architecture, de technologies et d'organisation des infrastructures. Ils tiennent compte à la fois des besoins fonctionnels exprimés, des contraintes opérationnelles de la DGRK et du contexte institutionnel et énergétique de la Ville-Province de Kinshasa.

a) **Approche modulaire et évolutive :** Le système doit être organisé en modules clairement identifiés correspondant aux grandes fonctions métiers (référentiels, assiette, contrôle, contentieux, SIG, reporting, etc.). Cette modularité facilite la maintenance, les évolutions futures et l'ajout progressif de nouvelles fonctionnalités sans remettre en cause l'ensemble du système.

b) **Centralisation de la donnée, décentralisation de l'accès :** Les données fiscales et géospatiales sont gérées dans des référentiels centraux uniques afin d'éviter les doublons et incohérences. En revanche, l'accès se fait de manière décentralisée depuis les différentes directions, centres de recettes et circonscriptions via des connexions sécurisées. Ce principe garantit l'unicité de l'information tout en permettant un travail simultané dans plusieurs sites.

c) **Intégration forte de la dimension géographique :** Le système intègre nativement des capacités SIG. La parcelle constitue l'unité de base, et la géolocalisation des objets fiscaux est considérée comme un élément structurant, non comme un simple accessoire cartographique. Les données fiscales et spatiales doivent pouvoir être croisées en permanence.

d) **Interopérabilité avec les systèmes partenaires :** Le SIGREC est conçu pour échanger des données avec les administrations et organismes partenaires (cadastre, DGI/NIF, SNEL, REGIDESO, urbanisme, notaires, etc.). Cette interopérabilité repose sur des interfaces normalisées (API, web services) afin d'éviter les ressaisies et de fiabiliser l'information.

e) **Sécurité, traçabilité et confidentialité :** La conception technique intègre dès l'origine la gestion des droits d'accès, l'authentification, la journalisation des actions des utilisateurs, la protection des données nominatives et la traçabilité des opérations. Ces exigences sont essentielles compte tenu de la sensibilité des informations fiscales et patrimoniales gérées par le système.

f) **Robustesse en contexte contraint :** L'architecture technique doit tenir compte des coupures électriques, de la qualité variable des connexions Internet et des difficultés d'accès à certains sites.

Cela implique notamment l'usage de solutions photovoltaïques pour l'alimentation électrique, des mécanismes de synchronisation différée et une capacité à fonctionner malgré des interruptions de réseau.

g) **Accessibilité et ergonomie :** Le système doit être accessible via des interfaces web et mobiles simples à utiliser par les agents, y compris ceux disposant d'un niveau limité en informatique. L'ergonomie constitue un facteur clé d'appropriation et donc de réussite du projet.

h) **h) Ouverture technologique et pérennité :** Les solutions techniques sont privilégiées lorsqu'elles reposent sur des standards ouverts, largement diffusés et maîtrisables localement. L'objectif est d'éviter toute dépendance excessive à un fournisseur unique et de faciliter le transfert de compétences aux équipes nationales.

Ces principes constituent le cadre de référence de l'architecture technique du SIGREC et guideront les choix détaillés qui seront effectués lors de la phase suivante de conception et de dimensionnement des équipements.

6.2 Architecture technique et applicative globale

L'architecture technique et applicative du SIGREC est organisée de manière à séparer clairement les rôles entre les différentes couches du système tout en assurant une forte intégration entre les fonctions fiscales et géographiques. Elle adopte une approche en architecture n-tiers, dans laquelle les couches présentation, métier et données sont distinctes mais interconnectées. Cette organisation garantit la performance, la sécurité et la facilité d'évolution du système.

a) Couche présentation : accès utilisateur et interfaces
Cette couche regroupe l'ensemble des interfaces utilisées par les différents profils d'utilisateurs :

- interface web pour les agents des directions centrales et provinciales ;
- interface web pour les centres de recettes et services déconcentrés ;
- portail contribuable pour les déclarations et consultations en ligne ;
- application mobile pour les équipes de recensement et de contrôle terrain.

Les interfaces sont accessibles via un navigateur web standard et fonctionnent dans un environnement connecté. L'application mobile permet la collecte d'informations géolocalisées, la prise de photos horodatées et, lorsque nécessaire, la synchronisation différée en cas de connexion Internet instable.

b) Couche métier : services applicatifs et modules fonctionnels
La couche métier regroupe les services applicatifs qui implémentent les différents modules décrits dans la conception fonctionnelle :

- gestion des référentiels (parcelles, bâtiments, unités, contribuables) ;
- gestion de l'assiette IF, IRL et TAS ;
- workflow d'enrôlement et de validation ;
- contrôle et inspection terrain ;
- calcul et liquidation ;
- émission des titres et notifications ;
- contentieux et sanctions ;
- reporting et tableaux de bord ;
- cartographie SIG et analyses spatiales ;
- aide à la décision.

Ces modules partagent un socle technique commun et s'appuient sur des règles de gestion centralisées. Ils fonctionnent de manière intégrée, ce qui évite la multiplication d'applications isolées et garantit la cohérence des données.

c) Couche d'intégration : échanges et interopérabilité
Cette couche joue le rôle de passerelle entre le SIGREC et les systèmes partenaires. Elle repose sur des interfaces normalisées permettant les échanges sécurisés de données, notamment avec :

- le cadastre et les services fonciers ;
- la DGI pour la gestion du NIF ;
- les régies et opérateurs techniques (SNEL, REGIDESO, etc.) ;
- les services d'urbanisme et d'habitat ;
- les notaires et instances judiciaires.

Les échanges se font par API, web services ou fichiers structurés, selon les capacités des systèmes existants. Cette couche d'intégration permet d'alimenter automatiquement le répertoire et de limiter les doubles saisies.

d) Couche données : bases fiscales et bases géospatiales
La couche de données constitue le socle informationnel du SIGREC. Elle comprend :

- une base de données fiscale contenant :
  - contribuables
  - parcelles
  - unités locatives
  - activités économiques
  - calculs d'assiette et liquidations
- une base de données géospatiale intégrant :
  - parcelles géoréférencées
  - bâtiments et unités géolocalisés
  - couches cartographiques de référence

Les deux bases sont étroitement liées par des identifiants uniques et par la référence parcellaire, ce qui permet de passer en permanence :

- d'une vue alphanumérique ;
- à une vue cartographique.

e) Services transversaux
Plusieurs services transversaux complètent l'architecture applicative :

- gestion des utilisateurs et des profils d'habilitation ;
- journalisation et traçabilité des opérations ;
- moteur de workflow ;
- moteur de notification (SMS, e-mail, portail) ;
- service de génération des états et rapports.

Ces services sont partagés par l'ensemble des modules, ce qui renforce la cohérence et simplifie la maintenance.

6.3 Architecture des données, interopérabilité et échanges

L'architecture des données du SIGREC vise à garantir l'unicité, la cohérence et la traçabilité de l'information fiscale et foncière. Elle organise les données autour de référentiels structurants et prévoit des mécanismes d'échange avec les systèmes d'information des administrations partenaires. L'objectif est d'éviter les ressaisies, de fiabiliser les informations et d'assurer une mise à jour continue du répertoire automatisé des contribuables.

a) Organisation générale des données
Les données du SIGREC sont structurées autour de plusieurs référentiels principaux :

- référentiel parcellaire ;
- référentiel des bâtiments et unités ;
- référentiel des contribuables (personnes physiques et morales) ;
- référentiel des activités économiques ;
- référentiel des impôts et taxes (IF, IRL, TAS).

Chaque référentiel est identifié par un identifiant unique et relié aux autres par des clés de liaison. La **parcelle** constitue l'objet pivot : elle relie les bâtiments, les unités locatives, les contribuables et les impositions.

Les données sont historisées, ce qui permet :

- de conserver les anciens propriétaires ;
- de suivre les mutations ;
- de retracer les valeurs précédentes d'assiette ou d'usage.

b) Données géospatiales et lien fiscal–spatial

L'architecture des données intègre nativement une base géospatiale. Les parcelles et bâtiments sont représentés par :

- des coordonnées GPS ;
- des polygones issus du cadastre ou de la photogrammétrie.

Chaque objet géographique est relié à son homologue fiscal par un identifiant commun. Ce lien permet de:

- cartographier les contribuables et les biens imposables ;
- détecter le bâti non déclaré ;
- analyser la répartition spatiale des recettes et de l'assiette.

c) Interopérabilité avec les administrations partenaires

Le SIGREC est conçu pour échanger des informations avec plusieurs institutions clés :

- **services cadastraux et circonscriptions foncières :** pour les références parcellaires et mutations foncières ;
- **DGI / système NIF :** pour l'attribution et la vérification des numéros d'identification fiscale ;
- **services d'urbanisme et d'habitat :** pour permis de construire, d'habiter ou de lotir ;
- **notaires et instances judiciaires :** pour ventes, successions, partages et décisions de justice ;
- **opérateurs techniques (SNEL, REGIDESO, etc.) :** pour repérage d'occupation effective des bâtiments.

Les échanges de données peuvent se faire par :

- API / web services sécurisés ;
- échanges de fichiers structurés (XML, CSV, etc.) ;
- synchronisations périodiques ou temps quasi réel.

d) Mécanismes d'alimentation et de mise à jour

Plusieurs canaux alimentent la base de données du SIGREC :

- recensement terrain via application mobile ;
- déclarations et auto-déclarations des contribuables ;
- saisies réalisées au guichet ;
- imports en provenance des systèmes partenaires.

Chaque mise à jour suit un workflow de validation et est historisée. Les modifications critiques (propriétaire, usage, superficie, assiette) nécessitent un niveau d'habilitation approprié.

e) Qualité des données et traçabilité

L'architecture des données intègre des mécanismes de contrôle :

- détection des doublons (NIF, parcelles, adresses) ;
- contrôles de cohérence (surface cadastrale vs surface déclarée) ;
- suivi des anomalies et corrections ;
- journalisation de toutes les opérations réalisées par les utilisateurs.

Ces dispositifs garantissent la qualité, la fiabilité et la valeur probante des données fiscales et spatiales du SIGREC.

6.4 Architecture d'infrastructure et interconnexion des sites

L'architecture d'infrastructure du SIGREC doit permettre à l'ensemble des services concernés de la DGRK d'accéder de manière fiable et sécurisée au système, tout en tenant compte de la dispersion géographique des structures et des contraintes énergétiques et de connectivité. Elle repose sur une organisation centralisée des ressources critiques et une interconnexion des sites distants via des réseaux sécurisés.

a) Organisation générale de l'infrastructure

L'infrastructure technique du SIGREC s'appuie sur :

- un **site central** hébergeant :
  - serveurs applicatifs ;
  - serveurs de base de données fiscales et géospatiales ;
  - services de sauvegarde et d'administration.
- des **sites utilisateurs distants** comprenant :
  - directions centrales et spécialisées ;
  - centres de recettes fiscales et non fiscales ;
  - services déconcentrés impliqués dans la gestion foncière et fiscale.

L'hébergement centralisé garantit :

- l'unicité des données ;
- la sécurisation des sauvegardes ;
- la facilité de maintenance et d'évolution ;
- une meilleure maîtrise des droits d'accès.

Les utilisateurs accèdent au système via des connexions réseau sécurisées, selon leur profil et leur périmètre d'intervention.

b) Interconnexion des sites distants

Le SIGREC doit être accessible aux principales structures administratives impliquées dans la gestion de l'impôt foncier, de l'IRL et de la taxe d'assainissement, notamment :

- **Direction de la Gestion des Impôts Provinciaux et Locaux :** (gestion IF et IRL pour personnes morales et grandes personnes physiques)
- **Direction du Contrôle et de l'Ordonnancement des Recettes Non Fiscales :** (gestion de la taxe d'assainissement pour personnes morales et grandes personnes physiques)
- **Direction de Recouvrement**
- **Direction des Recoupements et Recherches**
- **environ 32 centres de recettes fiscales et non fiscales**
- **circonscriptions foncières** pour l'impôt foncier (leur nombre exact sera précisé ultérieurement)

Ces différentes entités devront être interconnectées au site central par :

- liaisons Internet sécurisées (VPN)
- ou réseaux privés selon les possibilités existantes

L'architecture retenue doit permettre :

- un accès simultané de plusieurs sites
- la continuité de service malgré la dispersion géographique
- la remontée en temps quasi réel des informations de terrain

c) Alimentation électrique et résilience énergétique

Compte tenu du contexte local, l'alimentation électrique constitue un facteur critique de réussite du projet. L'infrastructure devra intégrer des solutions visant à renforcer la disponibilité en énergie, notamment :

- recours prioritaire à des **systèmes photovoltaïques** pour les sites distants et sensibles
- dispositifs hybrides si nécessaire (solaire + réseau + groupe électrogène)
- onduleurs et systèmes de protection pour postes de travail et équipements réseau

Ces dispositifs permettent :

- de limiter l'impact des coupures d'électricité

- d'assurer la continuité du service minimum
- de sécuriser les opérations d'enrôlement, de liquidation et de recouvrement

d) Postes de travail et équipements utilisateurs
Chaque site connecté devra être équipé de postes de travail adaptés à l'utilisation du SIGREC, comprenant :

- ordinateurs récents compatibles avec les interfaces web ;
- équipements réseau locaux (switchs, routeurs, points d'accès Wi-Fi si nécessaire) ;
- imprimantes pour l'édition locale des documents fiscaux ;
- smartphones ou tablettes pour les équipes de recensement et de contrôle terrain.

Ces équipements feront l'objet :

- d'un dimensionnement détaillé ;
- d'un cahier des charges technique ;
- dans la phase suivante du projet.

e) Dimensionnement et phasage
Le présent rapport définit l'architecture d'infrastructure et les principes d'interconnexion, mais **ne procède pas encore au dimensionnement détaillé** des équipements. Celui-ci sera réalisé dans la phase ultérieure, lors :

- de l'étude technique approfondie ;
- du cahier des charges des équipements à acquérir et à déployer.

Ce phasage permet d'arrêter d'abord l'architecture cible, puis d'adapter les capacités techniques en fonction :

- des besoins exprimés par les directions utilisatrices ;
- du nombre exact de sites impliqués ;
- des contraintes budgétaires et logistiques.

6.5 Sécurité, continuité de service et sauvegarde

La sécurité du système SIGREC et la continuité de son fonctionnement constituent des enjeux majeurs compte tenu de la sensibilité des données gérées et du rôle stratégique du répertoire fiscal automatisé dans la mobilisation des recettes provinciales. La conception technique intègre donc dès le départ des mécanismes destinés à protéger les données, à contrôler les accès, à tracer les opérations et à garantir la disponibilité du service même en cas d'incident.

a) Sécurité des accès et authentification
L'accès au système est strictement contrôlé. Chaque utilisateur dispose :

- d'un identifiant personnel ;
- d'un mot de passe robuste ;
- d'un profil d'habilitation correspondant à ses fonctions.

Les principaux principes appliqués sont :

- séparation des rôles (saisie, validation, contrôle, administration) ;
- limitation des droits au strict nécessaire (principe du "moindre privilège") ;
- désactivation rapide des comptes inactifs ou des agents mutés.

Lorsque les capacités techniques le permettent, l'architecture pourra intégrer des mécanismes avancés d'authentification (authentification forte, SSO, etc.).

b) Gestion des profils, rôles et habilitations
Le SIGREC intègre un module centralisé de gestion des profils et habilitations qui permet :

- de définir des familles de rôles par direction et par métier ;
- d'autoriser ou restreindre l'accès à certaines fonctions (lecture, saisie, validation, annulation) ;
- de contrôler l'accès aux informations nominatives et sensibles ;
- de tracer les attributions et retraits de rôles.

Cette gestion fine des habilitations limite les risques de fraude interne et renforce la responsabilité individuelle des utilisateurs.

c) Journalisation et traçabilité des opérations

Toutes les opérations sensibles réalisées dans le système font l'objet d'une traçabilité systématique. Le système conserve notamment :

- l'identification de l'utilisateur ;
- la date et l'heure de l'opération ;
- la nature de la modification effectuée ;
- les anciennes et nouvelles valeurs pour les champs critiques.

Cette journalisation permet :

- l'audit interne ;
- la reconstitution des événements en cas de litige ;
- la détection d'anomalies ou d'actions suspectes.

Elle constitue un élément clé de la crédibilité du système et de la protection de l'administration comme des contribuables.

d) Sécurité des données et confidentialité

Les données fiscales et foncières gérées par le SIGREC présentent un caractère sensible. À ce titre :

- les communications entre sites et le centre sont protégés par des mécanismes de chiffrement (VPN, HTTPS) ;
- les bases de données sont stockées dans un environnement contrôlé et sécurisé ;
- l'accès direct aux bases est strictement limité aux administrateurs habilités ;
- les extractions de données font l'objet de règles claires et d'autorisations spécifiques.

Le respect des règles de confidentialité s'applique tout particulièrement aux données nominatives des contribuables.

e) Sauvegarde et restauration des données

Un dispositif structuré de sauvegarde est mis en place afin de prévenir la perte de données en cas d'incident. Il comprend :

- des sauvegardes régulières des bases de données fiscales et géospatiales ;
- la conservation de plusieurs versions historiques ;
- la duplication des sauvegardes sur un support ou site distinct ;
- des procédures formalisées de restauration.

Ces sauvegardes sont testées périodiquement afin de vérifier leur validité et la capacité réelle de restauration.

f) Continuité de service et plan de reprise

Pour garantir la disponibilité du système, en particulier pendant les périodes critiques d'émission et de recouvrement, l'architecture prévoit :

- des équipements protégés contre les variations et coupures d'électricité ;
- un recours accru aux solutions photovoltaïques pour les sites distants ;
- la possibilité d'utiliser des mécanismes de synchronisation différée en cas de coupure réseau ;
- un **plan de reprise après incident** (PRA) définissant les procédures à suivre en cas de panne majeure.

Ces dispositifs visent à réduire au maximum :

- l'interruption du service ;
- la perte d'opérations ;
- l'impact sur les usagers et les recettes publiques.

7. Scénarios de mise en œuvre du répertoire SIGREC

La présente section examine plusieurs options pour la conception et la mise en œuvre du répertoire automatisé des contribuables. Différents scénarios techniques et organisationnels peuvent conduire à l'architecture cible décrite précédemment. Ils se distinguent par leur niveau d'intégration fonctionnelle, leur rythme de déploiement, leur degré d'urbanisation du système d'information ainsi que par le choix entre développement spécifique, adaptation d'une solution existante ou approche combinée.

L'objectif n'est pas d'arrêter définitivement un modèle unique, mais de présenter des scénarios réalistes, compatibles avec le contexte institutionnel, organisationnel et technique de la DGRK, puis d'en analyser les avantages, limites et conditions de réussite. Le scénario retenu sera ensuite précisé lors de la phase de conception détaillée et servira de base à la préparation des dossiers d'appel d'offres.

7.1 Tableau comparatif des scénarios de mise en œuvre du répertoire SIGREC

Tableau 7 : Comparatif des scénarios de mise en œuvre du répertoire SIGREC

Option	Description	Avantages	Limites	Estimation des coûts (Phase I)
Option 1 : Mise à niveau de l'existant ("patchwork")	Extension de l'application actuelle *e-DGRK* par ajout de modules externes (SIG, recensement mobile, gestion foncière), en réutilisant une grande partie du code existant.	- coûts et délais initiaux réduits - possibilité de livrer rapidement certaines fonctionnalités visibles - moindre effort de conduite du changement pour les utilisateurs actuels	- architecture monolithique ancienne difficile à faire évoluer - absence de base de données spatiale native - risques élevés d'instabilité et de performances insuffisantes - complexité accrue de maintenance et dette technique importante à moyen terme	**Faible à modéré≈ 100 000 – 250 000 USD**
Option 2 : Nouveau système intégré SIGREC	Conception et développement d'un nouveau système modulaire complet, reposant sur une base **PostgreSQL/PostGIS**, incluant application Web, application mobile et moteurs SIG et fiscalité intégrés.	- performances élevées - véritable architecture moderne et évolutive - intégration native de la géolocalisation et des référentiels parcellaires - meilleure interopérabilité avec cadastre, DGI, REGIDESO, SNEL, etc. - pérennité technologique et maîtrise locale à long terme	- délais plus longs (analyse, développement, tests, migration) - coûts initiaux plus importants - besoin d'une gouvernance projet forte et d'un encadrement technique robuste	**Modéré à élevé≈ 300 000 – 700 000 USD**
Option 3 : Solution "COTS" (progiciel du marché)	Acquisition d'un progiciel international spécialisé en gestion fiscale ou foncière, puis paramétrage et adaptation au contexte de la Ville-Province de Kinshasa.	- fonctionnalités déjà éprouvées ailleurs - existence d'un support éditeur et de mises à jour régulières - déploiement potentiellement plus rapide en environnement standard	- coûts d'acquisition et de licence très élevés - forte dépendance à long terme vis-à-vis de l'éditeur - adaptation au cadre légal et organisationnel local parfois limitée-risque d'inadéquation au contexte énergétique, réseau et capacité locale - TCO (coût total de possession) élevé et récurrent	**Élevé≈ 700 000 – 1 500 000 USD + licences annuelles**

Remarque : les montants sont des **ordres de grandeur indicatifs** pour la phase initiale et seront affinés lors du dimensionnement ultérieur.

7.2 Scénario recommandé

Option 2 : Développement d'un nouveau système intégré SIGREC

Justification

- **cohérence stratégique et technique**
  - seule option permettant une **vraie base parcellaire SIG**
  - architecture moderne, évolutive et interopérable
  - intégration native des besoins :
    - IF
    - IRL
    - TAS
    - contrôle terrain
    - géolocalisation
    - workflow et contentieux
- **meilleure appropriation locale**
  - technologie ouverte et maîtrisable localement
  - réduction de la dépendance à des licences étrangères
  - montée progressive des compétences des équipes DGRK
- **gestion maîtrisée des coûts sur le long terme**
  - coûts initiaux significatifs mais **TCO inférieur** aux solutions commerciales
  - absence d'abonnements obligatoires et de redevances éditeurs élevées
- **compatibilité avec le contexte opérationnel réel**
  - fonctionnement possible en :
    - environnement réseau instable
    - alimentation électrique à fiabiliser (photovoltaïque)
  - synchronisation différée
  - application mobile terrain intégrée
- **alignement avec les bailleurs et autorités**
  - approche :
    - progressive
    - modulaire
    - souveraine
    - basée sur standards ouverts
  - conforme aux bonnes pratiques internationales (TADAT, urbanisation SI).

Risques associés au non-choix de l'option recommandée

Le non-recours à l'option de développement d'un nouveau système intégré SIGREC exposerait la DGRK à plusieurs risques majeurs, notamment la persistance d'outils hétérogènes et peu performants, l'impossibilité d'intégrer pleinement la dimension géographique de l'assiette fiscale, ainsi qu'une dépendance accrue à des solutions propriétaires coûteuses et difficilement adaptables au contexte local. Il en résulterait une faible fiabilité du répertoire, une limitation des capacités de contrôle et de mobilisation des recettes, ainsi qu'un risque de remise en cause des investissements futurs faute d'architecture pérenne et évolutive.

8. Dispositions complémentaires

La présente section décrit les mesures d'accompagnement indispensables à la réussite du déploiement du répertoire automatisé des contribuables et du système SIGREC. Au-delà des aspects techniques et fonctionnels, la mise en œuvre effective du projet repose sur des conditions transversales incluant la formation des acteurs, l'appui logistique, la gestion du changement, l'adaptation éventuelle du cadre juridique ainsi que le suivi des performances. Ces dispositions visent à garantir une appropriation durable du système, à sécuriser les opérations et à maximiser l'impact du projet sur la mobilisation des recettes locales.

8.1 Renforcement des capacités et formation

La réussite du SIGREC repose en grande partie sur les compétences des équipes chargées de son exploitation. Un programme structuré de renforcement des capacités doit accompagner toutes les phases du projet. Il couvrira à la fois les aspects fonctionnels (fiscalité locale, gestion de l'assiette, recensement, contrôle) et techniques (utilisation de l'application, collecte mobile, SIG, administration du système).

La formation sera déployée selon une approche progressive comprenant :

- une formation des formateurs au niveau central
- la formation des utilisateurs finaux dans les directions et centres de recettes
- la formation spécialisée des administrateurs systèmes et bases de données
- des sessions dédiées aux équipes de recensement et contrôle terrain

Des supports pédagogiques seront produits, incluant manuels utilisateurs, vidéos courtes, fiches pratiques et procédures opérationnelles standard. La mise en place d'une formation continue est recommandée afin d'intégrer les nouveaux agents et d'accompagner l'évolution du système.

8.2 Gestion du changement et communication

La mise en œuvre du SIGREC implique une transformation importante des pratiques professionnelles. Elle modifie les méthodes de travail, renforce la traçabilité et introduit de nouveaux outils numériques. Une stratégie de gestion du changement est donc indispensable pour favoriser l'adhésion des utilisateurs et limiter les résistances.
Cette stratégie comprendra notamment :

- une communication régulière sur les objectifs et bénéfices du projet
- la désignation de points focaux "SIGREC" dans chaque direction et centre
- l'implication des utilisateurs clés dès les phases de test et de validation
- l'identification et la gestion des impacts organisationnels
- la prise en compte des retours du terrain pour ajuster progressivement les outils

Une attention particulière devra être accordée à la valorisation des agents impliqués dans le recensement et le contrôle, afin d'encourager l'appropriation du dispositif.

8.3 Appui logistique et équipements

La mise en œuvre opérationnelle du SIGREC nécessite un appui logistique adapté. Celui-ci inclut :

- postes de travail pour les utilisateurs dans les directions et centres de recettes
- tablettes ou smartphones pour le recensement et les contrôles terrain
- équipements réseau et solutions d'interconnexion des sites
- imprimantes pour l'édition locale des documents fiscaux

Compte tenu du contexte énergétique, il est recommandé de renforcer l'alimentation électrique des sites prioritaires par des solutions photovoltaïques complétées, au besoin, par des dispositifs hybrides. Le dimensionnement précis des équipements fera l'objet d'une phase ultérieure et sera intégré dans les dossiers d'appel d'offres.

8.4 Aspects juridiques et réglementaires

Le SIGREC doit évoluer dans un cadre juridique sécurisé. Sa mise en œuvre s'appuie sur les textes existants relatifs à la fiscalité locale, à la gestion foncière et à la protection des données. Toutefois, certaines adaptations réglementaires pourront s'avérer nécessaires, notamment pour :

- encadrer l'usage systématique de la géolocalisation dans la gestion de l'assiette ;
- consolider l'obligation de déclaration et d'identification des contribuables ;
- sécuriser les échanges de données entre institutions partenaires ;
- formaliser la valeur probante des informations contenues dans le répertoire.

Une attention particulière doit être accordée à la confidentialité des données nominatives et patrimoniales, en conformité avec les principes de protection des données personnelles et de respect des droits des contribuables.

8.5 Suivi, évaluation et indicateurs de performance

La mise en œuvre du SIGREC doit être accompagnée d'un dispositif structuré de suivi-évaluation permettant de mesurer les progrès réalisés, d'identifier les écarts et d'ajuster les actions correctives. Ce dispositif vise à apprécier non seulement les résultats techniques du projet, mais aussi ses impacts sur l'élargissement de l'assiette fiscale, la fiabilité des répertoires et l'amélioration du recouvrement.

Le suivi-évaluation reposera sur plusieurs catégories d'indicateurs :

- **indicateurs de mobilisation de l'assiette et des recettes**, mesurant la progression du nombre de contribuables et des bases imposables ;
- **indicateurs de qualité des données**, évaluant l'exhaustivité, la fiabilité et la géolocalisation des informations ;
- **indicateurs opérationnels**, renseignant sur l'activité des équipes (recensement, traitement des dossiers, contrôles) ;
- **indicateurs de service**, liés aux performances du système (disponibilité, délais, incident) ;
- **indicateurs d'appropriation**, relatifs à la formation et à l'utilisation effective du système par les agents.

Des bilans périodiques permettront d'apprécier les impacts du projet en termes d'élargissement de l'assiette, de fiabilisation des répertoires et de renforcement du recouvrement. Les résultats du suivi-évaluation alimenteront le pilotage stratégique de la DGRK ainsi que les échanges avec les autorités provinciales et les partenaires techniques et financiers.

8.5.1 Tableau de bord opérationnel

Le SIGREC devra intégrer un tableau de bord interactif affichant les principaux indicateurs clés de performance (KPI), accessibles aux décideurs et responsables opérationnels. Ce tableau de bord permettra un pilotage continu de l'assiette, du recensement, de la qualité des données et des performances du système.

Tableau 8 : Indicateurs clés de performance (KPI)

Indicateur de performance (KPI)	Objectif cible à 12 mois	Fréquence de mesure	Responsable du suivi
Taux de couverture de l'assiette (réel/potentiel)	70 %	Trimestrielle	Direction des impôts provinciaux et locaux
Taux d'exhaustivité du répertoire (parcelles recensées)	80 %	Trimestrielle	Équipe recensement/VFE
Taux de fiabilité des données (NIF + géolocalisation valide)	95 %	Mensuelle	Bureau qualité des données
Taux de géolocalisation des parcelles enregistrées	90 %	Mensuelle	Unité SIG
Réduction des doublons (SIGREC vs e-DGRK et autres bases)	90 %	Semestrielle	Bureau qualité des données

Indicateur de performance (KPI)	Objectif cible à 12 mois	Fréquence de mesure	Responsable du suivi
Délai moyen d'intégration des mutations cadastrales	< 24 h	Quotidienne	Direction informatique
Nombre de nouvelles parcelles enregistrées	+20 %	Mensuelle	Centres de recettes
Nombre d'unités locatives identifiées	+30 %	Trimestrielle	Directions opérationnelles
Taux d'utilisation du portail contribuable	40 % des déclarations	Trimestrielle	Direction services au contribuable
Nombre de contrôles terrain réalisés	+25 %	Mensuelle	Directions de contrôle
Taux de régularisation après contrôle	≥ 60 %	Trimestrielle	Direction de recouvrement
Disponibilité du système SIGREC	≥ 98 %	Mensuelle	Direction informatique
Taux d'incidents critiques non résolus > 48 h	0 %	Mensuelle	Support technique
Taux d'agents formés et certifiés SIGREC	≥ 85 %	Semestrielle	Cellule formation
Taux de mise à jour des dossiers contribuables inactifs/actifs	≥ 90 %	Trimestrielle	Directions fiscales

Les valeurs cibles pourront être confirmées et ajustées après la première année de mise en œuvre.

8.5.2 Mécanismes de reporting

Le dispositif de suivi-évaluation reposera sur :

- des tableaux de bord automatisés intégrés au SIGREC
- des rapports périodiques consolidés par la cellule projet
- des réunions trimestrielles d'analyse de performance
- des audits ponctuels de qualité des données et des processus

Ces mécanismes permettront d'instaurer une culture de pilotage par la donnée et d'assurer la transparence des résultats du projet.

8.6 Risques et hypothèses

La mise en œuvre du dispositif de suivi-évaluation du SIGREC repose sur un certain nombre d'hypothèses et doit tenir compte de risques susceptibles d'en affecter la performance. Les identifier en amont permet d'anticiper des mesures d'atténuation et d'assurer la fiabilité des résultats produits.

8.6.1 Hypothèses de réussite

Le dispositif suppose notamment :

- la disponibilité régulière des données provenant des directions et centres de recettes ;
- l'engagement actif des responsables sectoriels dans la production et validation des indicateurs ;
- la mise à disposition d'une équipe dédiée au suivi-évaluation et à la qualité des données ;
- la stabilité minimale du système informatique et des réseaux d'interconnexion ;
- la mise en œuvre effective des formations des utilisateurs et administrateurs ;
- l'existence d'un appui institutionnel soutenu pour l'exploitation des résultats produits.

Ces hypothèses constituent des prérequis essentiels pour garantir la pertinence et la continuité du suivi-évaluation.

8.6.2 Principaux risques identifiés

La matrice ci-dessous synthétise les principaux risques susceptibles d'affecter la mise en œuvre du dispositif de suivi-évaluation du SIGREC, leurs impacts potentiels ainsi que les mesures d'atténuation proposées.

Tableau 9 : Principaux risques

Risque identifié	Impact potentiel sur le projet	Mesures d'atténuation proposées
Qualité insuffisante des données collectées	Indicateurs biaisés, décisions inadaptées, perte de crédibilité du système	Mise en place d'un bureau "qualité des données", contrôles automatiques, validation hiérarchique
Retard ou absence de transmission des informations par certains services	Rupture du suivi, rapports incomplets, pilotage affaibli	Procédures formalisées de remontée d'information, calendrier obligatoire, sanctions et incitations
Résistance au changement des utilisateurs	Sous-utilisation du SIGREC, contournement des procédures, faible impact du projet	Programme d'accompagnement au changement, communication, valorisation des bonnes pratiques
Insuffisance de ressources humaines qualifiées pour le suivi-évaluation	Faible capacité d'analyse, retard dans la production des rapports, dépendance à l'assistance externe	Formation ciblée, constitution d'une cellule dédiée S&E, plan de renforcement progressif des compétences
Pannes d'électricité et interruptions réseau	Interruption de la saisie, perte de données, retards d'alimentation	Équipements photovoltaïques, onduleurs, synchronisation différée, politique de sauvegarde stricte
Non-respect des procédures de mise à jour des bases	Décalage entre la réalité et le répertoire fiscal, assiette faussée	Manuel de procédures, audits périodiques, traçabilité renforcée des mises à jour
Défaillance ou indisponibilité du système SIGREC	Paralysie temporaire du suivi, perte d'informations, baisse de confiance des utilisateurs	Plan de reprise d'activité, sauvegardes régulières, supervision technique permanente
Faible exploitation des résultats produits par les KPI	Perte d'intérêt pour le S&E, décisions non appuyées sur la donnée	Réunions trimestrielles de performance, diffusion de tableaux de bord aux décideurs, obligation de reporting
Modifications réglementaires non anticipées	Indicateurs obsolètes, inadéquation juridique	Veille juridique, mise à jour périodique des référentiels et des indicateurs
Turn-over élevé du personnel utilisateur	Perte de compétences, rupture dans les pratiques	Programme continu de formation et recertification, documentation accessible

9. Cadre de mise en œuvre et de suivi des actions planifiées

Compte tenu de la révision du calendrier du projet KIN-ELENDA et de la fixation de la date de clôture du contrat du consortium à fin juin 2026, le présent cadre de mise en œuvre vise à prioriser les actions effectivement réalisables dans le délai restant, tout en identifiant de manière explicite les activités structurantes à poursuivre au-delà du projet.

Ce cadre précise :

- les instruments opérationnels mobilisables à court terme ;
- les acteurs impliqués et leurs responsabilités effectives ;
- les modalités de financement compatibles avec l'échéance contractuelle ;
- ainsi que les mécanismes de suivi-évaluation, adaptés à une phase de mise en place initiale du répertoire automatisé des contribuables dans le cadre du SIGREC.

L'objectif n'est pas de couvrir l'intégralité du cycle de développement et de généralisation du SIGREC, mais de poser un socle technique, institutionnel et opérationnel solide, permettant la continuité et l'extension du dispositif après la clôture du projet.

9.1 Instruments de mise en œuvre

Dans la phase restante (janvier-juin 2026), la mise en œuvre des actions prioritaires repose sur un ensemble volontairement limité d'outils, afin de garantir un pilotage clair, une exécution coordonnée et une redevabilité renforcée.
Deux instruments structurants seront élaborés et utilisés :

1. une feuille de route opérationnelle et budgétisée, centrée sur le périmètre réalisable avant fin juin 2026 ;
2. un plan de communication ciblé, orienté vers l'appropriation institutionnelle et la gestion du changement.

9.1.1 Feuille de route opérationnelle et budgétisée

La feuille de route opérationnelle et budgétisée constitue le document de référence pour la période restante. Elle présente :

- les activités à mettre en œuvre jusqu'à la clôture du projet ;
- les résultats intermédiaires attendus ;
- les indicateurs de performance associés ;
- le chronogramme d'exécution ;
- les structures responsables ;
- les coûts estimatifs ;
- les sources de financement ;
- ainsi que l'échéancier de décaissement.

Elle distinguera explicitement :

- les actions réalisables avant fin juin 2026, faisant l'objet d'un suivi opérationnel et d'un reporting ;
- les actions structurantes hors délai, identifiées comme recommandations pour une phase de continuité post-projet.

9.1.2 Plan de communication

La réussite de la phase actuelle repose autant sur la qualité des livrables que sur une communication claire, régulière et structurée entre les parties prenantes. Le plan de communication vise à :

- informer les acteurs institutionnels et les contribuables ;
- accompagner la gestion du changement ;
- améliorer l'acceptabilité des actions liées au recensement et à l'usage du NIF ;
- soutenir l'adhésion des services concernés.

Il permettra aussi d'assurer une circulation fluide et fiable de l'information entre les instances du projet (Cellule Infrastructures, Ministère provincial des Finances et du Numérique, DGRK, consortium CCM/BPRES), de clarifier les objectifs, étapes clés et résultats attendus, et de mobiliser les acteurs impliqués ainsi que les autres parties prenantes (contribuables, opérateurs économiques) sur leurs obligations fiscales et sur les changements introduits.

9.1.3 Acteurs de mise en œuvre

La mise en œuvre des actions prioritaires retenues dans la feuille de route repose sur un nombre limité d'acteurs institutionnels et techniques, dont l'implication conditionne directement l'atteinte des résultats attendus à court terme.
Dans un calendrier contraint, les responsabilités sont recentrées sur :

- la décision et l'arbitrage rapides ;
- la mobilisation opérationnelle des services clés ;
- la coordination étroite avec le consortium d'exécution.

Les autres parties prenantes, bien que stratégiques pour la pérennisation du dispositif, interviennent principalement à titre de partenaires de continuité post-projet.

9.1.4 Leadership politique et pilotage stratégique à court terme

Les résistances au changement et les réticences à la mise à disposition des informations nécessaires à la structuration du répertoire constituent un facteur de ralentissement majeur. Dans le délai restant, ces obstacles ne peuvent être levés que par un leadership politique clair, visible et orienté vers des résultats mesurables.

À ce titre, l'implication active :

- du Ministre provincial en charge des Finances, de l'Économie et du Numérique ;
- ainsi que du Chargé de mission auprès de la DGRK,

est déterminante pour donner les orientations, arbitrer les blocages, légitimer les décisions techniques et accélérer l'exécution des actions prioritaires. À défaut, le risque est élevé de clôturer le projet sans consolidation suffisante des acquis.

9.1.5 Comité de pilotage et articulation avec les cadres nationaux de réforme

La numérisation des finances publiques provinciales et le renforcement de la mobilisation des recettes locales s'inscrivent dans les orientations nationales de réforme et de décentralisation financière. La supervision stratégique globale relève des instances nationales, mais l'échéance rapprochée impose un pilotage de proximité, adapté aux réalités opérationnelles de la Ville-Province de Kinshasa.
Il est recommandé que :

- le cadre national de pilotage de la réforme soit informé et associé aux orientations générales ;
- et qu'un dispositif provincial et local de pilotage, sous l'autorité du Gouverneur de province et présidé par le Ministre provincial compétent, assure le suivi rapproché des actions réalisées jusqu'à fin juin 2026.

Cette articulation garantit la cohérence avec les réformes nationales tout en permettant une prise de décision rapide au niveau provincial.

9.1.6 Administration fiscale provinciale (DGRK)

La DGRK constitue l'acteur opérationnel central de la feuille de route. Sur la période allant jusqu'à fin juin 2026, son rôle porte prioritairement sur :

- la contribution à la définition et à la validation des référentiels de base ;
- la mise à disposition des données existantes nécessaires à la structuration initiale du répertoire ;
- la participation aux actions de recensement ciblé, nettoyage et consolidation des données ;
- l'appropriation progressive des outils, procédures et pratiques introduits.

Sans implication effective des services de la DGRK, les résultats resteront limités, quelle que soit la qualité des solutions techniques produites.

9.1.7 Services fonciers et de l'habitat

Les services provinciaux du cadastre, de conservation des titres immobiliers et de l'habitat sont essentiels pour la fiabilité des informations relatives aux contribuables concernés par l'IF, l'IRL et la taxe d'assainissement.
Dans le délai restant, leur contribution sera ciblée sur :

- la mise à disposition des données disponibles sous format exploitable ;
- l'appui à la validation croisée des informations foncières ;
- la contribution à la définition des mécanismes d'interopérabilité à mettre en œuvre ultérieurement.

L'informatisation complète de leurs répertoires relève d'une phase de continuité post-projet et ne constitue pas un prérequis bloquant pour le socle initial.

9.1.8 Partenaires du projet et acteurs externes

Les partenaires institutionnels et techniques interviennent en appui à la mise en œuvre et à la sécurisation du processus, notamment :

- la Cellule Infrastructures (maître d'ouvrage et interface avec le bailleur) ;
- la CDUK (partenaire opérationnel) ;
- la Banque mondiale (suivi stratégique et validation des orientations majeures) ;
- le consortium CCM–BPRES (exécution technique et assistance opérationnelle).

La coordination entre ces acteurs devra privilégier la continuité des activités prioritaires, la levée rapide des contraintes et une mobilisation pragmatique des moyens nécessaires à la matérialisation des acquis.

9.2 Mécanismes de suivi-évaluation

Le suivi-évaluation vise, dans un délai contraint, à garantir l'exécution effective des actions prioritaires, la production de résultats intermédiaires vérifiables et la redevabilité vis-à-vis des autorités provinciales et du bailleur. Le dispositif est conçu comme un outil de pilotage opérationnel centré sur la période janvier–juin 2026.

9.2.1 Dispositif et principes de suivi-évaluation

Le suivi repose sur :

- la vérification régulière de l'avancement ;
- l'appréciation des résultats intermédiaires ;
- l'identification rapide des écarts et mesures correctives ;
- un reporting périodique.

Il sera fondé sur un nombre limité d'indicateurs directement mesurables avant fin juin 2026, portant notamment sur la structuration du répertoire, la qualité des données, l'implication des services et la disponibilité du socle SIGREC.

9.2.2 Outils de suivi-évaluation

Le dispositif s'appuiera sur :

- une matrice de programmation et de reporting ;
- une matrice de mesure des résultats (activités, indicateurs, livrables) ;
- un cadre logique simplifié.

Ces outils seront complétés par un tableau de bord opérationnel SIGREC, des rapports d'avancement, des matrices de suivi et des contrôles ciblés de qualité des données.

9.2.3 Instance de suivi-évaluation

Le suivi-évaluation sera assuré par un dispositif provincial et local de pilotage, à mettre en place ou à mobiliser s'il existe déjà, en coordination avec la Cellule Infrastructures, la CDUK et le consortium CCM–BPRES. Il assure le suivi des actions, la validation des livrables clés, les recommandations opérationnelles et le reporting à la Banque mondiale.

9.2.4 Acteurs et responsabilités du suivi-évaluation

Le suivi opérationnel est assuré par un comité technique placé sous l'autorité du Ministre provincial en charge des Finances et du Numérique, chargé de coordonner le suivi, superviser les rapports, veiller à l'implication des structures et rendre compte périodiquement au dispositif de pilotage.

9.3 Conditions de succès et facteurs de risque

La réussite de la feuille de route sur la période janvier–juin 2026 dépend de conditions clés et reste exposée à des risques liés au contexte institutionnel, opérationnel et temporel. Leur anticipation est essentielle pour sécuriser les résultats intermédiaires avant la clôture du projet.

9.3.1 Conditions de succès

Les conditions de succès incluent notamment :

- leadership politique affirmé et portage par la DGRK,
- appropriation des services clés et mobilisation des agents,
- disponibilité en temps utile des ressources et décaissements compatibles,
- moyens techniques, logistiques et énergétiques minimums,
- cadre institutionnel suffisamment stabilisé pour le partage de données et le NIF,
- capacité d'arbitrage rapide entre actions à réaliser et actions à reporter.

9.3.2 Facteurs de risque

Tableau 10 : Analyse des risques

N°	Énoncé du risque	Occurrence	Incidence	Criticité
1	Non-adhésion des acteurs et résistance au changement	3	3	9
2	Défaillance des capacités techniques et/ou humaines	2	2	4
3	Retards dans les procédures d'acquisition et de mobilisation des moyens	2	3	6
4	Contraintes financières, logistiques et énergétiques	1	2	2

Occurrence (Probabilité de survenance) : 1 : Faible ; 2 : Moyenne ; 3 : Elevé.
Incidence (impact): 1 : Faible ; 2 : Moyenne ; 3 : Elevé.
Criticité = (Occurrence x Incidence) : 1 - 2 : Faible ; 3 - 4 : Moyenne ; 6 - 9 : Elevé.

9.3.3 Mesures de mitigation des risques

Tableau 11 : Mesures de mitigation

N°	Risque	Stratégie	Activités prévues
1	Résistance au changement	Gestion du changement	Plan de communication, sensibilisation ciblée
2	Capacités insuffisantes	Renforcement ciblé	Appui technique, accompagnement des équipes
3	Retards d'acquisition	Accélération	Anticipation, validation rapide TDR/DP/DAO
4	Contraintes financières/énergie	Priorisation	Solutions alternatives, appui ciblé partenaires

9.4 Feuille de route

La feuille de route distingue :

- une phase de mise en place initiale, réalisable et couverte par le projet jusqu'à fin juin 2026 ;
- une phase de continuité et d'extension à conduire après la clôture, sur la base des acquis consolidés.

9.4.1 Principes de structuration

La feuille de route repose sur :

- réalisme temporel ;
- approche "socle fonctionnel" ;
- progression par étapes ;

- avancement modulaire ;
- responsabilisation claire ;
- distinction explicite phase projet / phase post-projet.

9.4.2 Chronologie indicative (recalée)

Tableau 12 : Chronologie de mise en œuvre

Phase	Période	Résultats attendus principaux
Phase 1 – Cadrage et gouvernance	Jan–fév 2026	Gouvernance clarifiée, feuille de route validée
Phase 2 – Référentiels de base	Fév–avr 2026	Répertoire structuré, données consolidées, doublons réduits
Phase 3 – Développements et tests	Mar–mai 2026	Modules prioritaires adaptés, tests réalisés
Phase 4 – Mise en service initiale	Mai–juin 2026	Socle SIGREC en service, appropriation pilote, transfert des acquis

Les phases de généralisation et d'optimisation avancée relèvent du post-projet.

9.4.3 Activités de continuité post-projet

Sont identifiées comme structurantes mais hors délai :

- généralisation au niveau des communes de la province,
- interconnexions complètes ;
- extension du périmètre fiscal ;
- informatisation exhaustive des services fonciers/habitat ;
- optimisation recouvrement/contrôle ;
- dispositifs analytiques avancés.

9.4.4 Cadre financier, soutenabilité et valeur ajoutée

La budgétisation est limitée à la phase projet. Les coûts post-projet sont indicatifs, sans engagement immédiat. Les estimations distinguent :

- coûts de mise en place du socle ;
- coûts récurrents ;
- projection indicative du TCO.

Le financement de la phase projet couvre l'AT, la consolidation des données, les développements prioritaires, la communication, et les besoins techniques/logistiques. La programmation détaillée figure dans la feuille de route budgétisée.

Distinction CAPEX / OPEX

- CAPEX : acquisitions d'équipements et infrastructures.
- OPEX : fonctionnement, maintenance, exploitation.

Tableau 13 : Estimation indicative CAPEX / OPEX

Catégorie	Équipements / services	Type	Périmètre	Estimation indicative en USD
Infrastructures SI	Serveurs, stockage, réseau	CAPEX	Socle SIGREC	60 000 – 80 000
	Hébergement, sauvegardes	OPEX	Exploitation initiale	10 000 – 20 000 /an
Postes utilisateurs	Ordinateurs	CAPEX	Services centraux/pilotes	40 000 – 60 000
Équipements mobiles	Tablettes et accessoires	CAPEX	Recensement ciblé	30 000 – 40 000
Interconnexion	Réseau, connectivité sécurisée	CAPEX	Sites pilotes	15 000 – 30 000
	Abonnements internet	OPEX	Fonctionnement	5 000 – 10 000 /an

Catégorie	Équipements / services	Type	Périmètre	Estimation indicative en USD
Sécurité énergétique	Photovoltaïque, onduleurs, batteries	CAPEX	Sites critiques	75 000 – 100 000
	Maintenance	OPEX	Exploitation	7 000 – 10 000 /an
Sécurité SI	Pare-feu, contrôle d'accès	CAPEX	Protection	10 000 – 25 000
	Support/mises à jour	OPEX	Exploitation	7 000 – 10 000 /an

Les coûts récurrents (hébergement, support, énergie, renouvellements) sont documentés pour préparer la continuité. Une projection indicative du TCO est proposée pour éclairer les décisions futures et sera affinée lors des phases ultérieures.

Principe de prudence
Le cadre financier vise à sécuriser les acquis sans dépendance excessive et sans engagement implicite au-delà du contrat. Les équipements acquis sont transférables aux autorités provinciales.

10. Conclusion et perspectives

10.1 Conclusion

Le diagnostic réalisé montre que l'actuel répertoire des contribuables « e-DGRK » ne répond plus aux exigences d'une gestion fiscale moderne. Son architecture, centrée sur des données non géolocalisées et faiblement interopérables, limite la fiabilité de l'assiette, l'actualisation des informations et la lutte contre la fraude. Il ne permet pas d'accompagner la dynamique urbaine de Kinshasa ni les réformes engagées en matière de mobilisation des recettes.

La transition vers un **système intégré, géolocalisé et interopérable** constitue donc une étape incontournable. L'option consistant à développer un **nouveau SIGREC/DGRK** apparaît comme la solution la plus pérenne, la plus évolutive et la mieux adaptée au contexte institutionnel et opérationnel. Elle nécessite un investissement initial significatif, principalement orienté vers :

- la constitution d'un répertoire parcellaire fiable et géolocalisé ;
- la refonte du modèle de données et de l'architecture technique ;
- la mise en place d'outils de recensement mobile et de contrôle terrain.

Cet investissement est cependant justifié par les gains attendus en termes d'élargissement de l'assiette, d'amélioration de l'équité fiscale et de sécurisation durable des recettes provinciales.

10.2 Synthèse des résultats attendus

La mise en œuvre du SIGREC permettra notamment :

- la sécurisation de l'assiette fiscale grâce à la géolocalisation des parcelles et à la traçabilité des mutations ;
- la réduction des fraudes et sous-déclarations, par le croisement systématique avec les données cadastrales et techniques (eau, électricité, autorisations, etc.) ;
- l'augmentation du taux de couverture des contribuables, avec un objectif réaliste supérieur à 70 % à moyen terme ;
- l'amélioration de l'équité fiscale, la taxation reposant sur des paramètres mesurés (surface, usage, situation d'occupation) ;
- l'accroissement substantiel des recettes locales, permettant de renforcer la capacité d'investissement public ;
- le passage à une gouvernance par la donnée, grâce aux tableaux de bord, à la cartographie et aux analyses spatiales.

Le projet présente ainsi un retour sur investissement élevé, tout en contribuant à la modernisation de l'administration fiscale provinciale.

10.3 Prochaine étape

10.3.1 Validation institutionnelle

La première étape consiste à obtenir une validation formelle par les autorités compétentes portant sur :

- l'option de mise en œuvre du SIGREC ;
- le modèle conceptuel de données ;
- le principe d'interfaçage avec le cadastre et les autres institutions partenaires.

Cette validation constitue le point de départ officiel du projet.

10.3.2 Mobilisation des ressources

La mise en œuvre nécessite ensuite la mobilisation progressive des moyens financiers, humains et logistiques, notamment pour :

- l'amélioration des conditions de travail (énergie, interconnexion, postes de travail) ;
- la préparation et l'organisation du recensement géolocalisé des parcelles et des unités imposables;
- la constitution d'une équipe projet pluridisciplinaire, associant fiscalité, SIG et informatique.